ଅଷ୍ଟମ ଅଧ୍ୟାୟ

ପରିବହନ, ଯୋଗାଯୋଗ ଏବଂ ବାଣିଜ୍ୟ

J7C3Y1

ଦେଶର ଆର୍ଥିକ ଅବସ୍ଥାରୁ ସୁଦୃଢ଼ କରିବାରେ ସହାୟକ ହେଉଥିବା ସମସ୍ତ ସମ୍ବଳକୁ ଆଧାରିକ ସଂରଚନା (Infrastsuctiene) କୁହାଯାଏ । ଉତ୍ତମ ଆଧାରିକ ସଂରଚନା ମଧ୍ୟରେ ପରିବହନ, ରେଳପଥ, ସଡ଼କପଥ, ବନ୍ଦର, ବିମାନ ଚଳାଚଳ ଇତ୍ୟାଦି । ଯୋଗାଯୋଗ (ଟେଲିଫୋନ, ମୋବାଇଲ ଫୋନ୍, ଇଣ୍ଟରନେଣ୍ଟ ଡାକ ଇତ୍ୟାଦି) ଏବଂ ବିଦ୍ୟୁତ ପରିବହନ ଓ ବିତରଣ ଦେଦେଶର ଅର୍ଥନୈତିକ ବିକାଶ କ୍ଷେତ୍ରରେ ନିର୍ଣ୍ଣାୟକ ଗ୍ରହଣ କରିଥାନ୍ତି ।

ପରିବହନ :

ଭାରତ ଏକ ବିଶାଳ ଦେଶ । ସାମାଜିକ ସମ୍ବଳ ବୃଦ୍ଧି, ତ୍ୱରାନ୍ୱିତ ଆର୍ଥିକ ପ୍ରଗତି, ଦେଶର ସୁଦୃଢ଼ ପ୍ରତିରକ୍ଷା ବ୍ୟବସ୍ଥା ତଥା ଆଞ୍ଚଳିକ ସଂହତି ରକ୍ଷା ପାଇଁ ପରିବହନ ଯୋଗାଯୋଗ ଓ ବାଣିଜ୍ୟ ଏକାନ୍ତ ଆବଶ୍ୟକ । ଯାତ୍ରୀ ବା ଜିନିଷ ପତ୍ରଗୁଡ଼ିକୁ ଗୋଟିଏ ସ୍ଥାନରୁ ଅନ୍ୟ ସ୍ଥାନକୁ ବହନ କରି ନେବା ପ୍ରକ୍ରିୟାକୁ ପରିବହନ କୁହାଯାଏ । ଏଗୁଡ଼ିକୁ ଯେଉଁଥିରେ ବହନ କରାଯାଏ ତାହାକୁ ଯାନ ବା ବାହନ କୁହାଯାଏ । ଅତୀତରେ ମଣିଷ ନିଜେ ନିଜର ଜିନିଷ ପତ୍ର ମୁଣ୍ଡରେ ବା କାନ୍ଧରେ ଭାରସାହାଯ୍ୟରେ ବୋହି ନେଉଥିଲା । କାଳକ୍ରମେ ଗୃହପାଳିତ ପଶୁ ଯଥା, ଗଧ, ଘୋଡ଼ା, ଖଚର, ବଳଦ ଓ ମଇଁଷି ପ୍ରଭୃତିକୁ ଭାରବାହୀ ପଶୁଭାବରେ ବ୍ୟବହାର କଲା । ଚକର ଉଦ୍ଭାବନ ପରେ ବଳଦଗାଡ଼ି ଓ ଘୋଡ଼ାଗାଡ଼ିରେ ମଧ୍ୟ ଜିନିଷପତ୍ର ବୋହି ନେଇପାରିଲା ।

ଭାରତର ପ୍ରତ୍ୟେକ ପ୍ରାନ୍ତରେ ଏବେ ମଧ୍ୟ ପୁରୁଷ ସ୍ତ୍ରୀ କିମ୍ବା ପିଲାମାନେ ମୁଣ୍ଡ ଉପରେ ଲଦି ବା ଭାରକାନ୍ଧେଇ ଖାଦ୍ୟଶସ୍ୟ, ଜାଳେଣି କାଠ କିମ୍ବା ଅନ୍ୟାନ୍ୟ ଘରକରଣା ଜିନିଷ ରାସ୍ତା ଘାଟରେ ବୋହି ନେଉଥିବାର ଦୃଶ୍ୟ ଦେଖିବାକୁ ମିଳେ । ମଣିଷ ହାତ ଟଣା ରିକ୍ସା ଓ ଶଗଡ଼ ଗାଡ଼ି, ସାଇକେଲ, ରିକ୍ସା, ଟ୍ରଲି ଆଦି ଏବେ ମଧ୍ୟ ପ୍ରଚଳିତ ହେଉଛି ।

ଏବେ କିନ୍ତୁ ପରିବହନ ଯାନ୍ତ୍ରିକ ଶକ୍ତି ଉପରେ ଅତ୍ୟଧିକ ଭାବରେ ନିର୍ଭରଶୀଳ । ପରିବହନ ବ୍ୟବସ୍ଥା ମନୁଷ୍ୟ ଶରୀରର ରକ୍ତ ସଂଚାଳନ ସହ ତୁଳନୀୟ । ରକ୍ତ ସଂଚଳାନ ମନୁଷ୍ୟ ଜୀବନ ପାଇଁ ଯେପରି ଗୁରୁତ୍ୱପୂର୍ଣ୍ଣ ଦେଶର ଅର୍ଥନୀତି ସୁପରିଚାଳନା ପାଇଁ ପରିବହନ ବ୍ୟବସ୍ଥା ସେହି ଭଳି ମହତ୍ୱ ପୂର୍ଣ୍ଣ । ପରିବହନ ଦ୍ୱାରା ଉତ୍ପାଦନ ଓ ଉପଭୋକ୍ତାମାନଙ୍କ ମଧ୍ୟରେ ସଂଯୋଗ ସ୍ଥାପିତ ହୁଏ । ଜିନିଷ ପତ୍ର ନେବା ଆଣିବା ଆଜିର ଦ୍ରୁତ ପରିବହନ ବ୍ୟବସ୍ଥା ଦ୍ୱାରା ଅଧିକ ସୁବିଧାରେ ହୋଇପାରୁଛି । ପରିବହନ ବ୍ୟବସ୍ଥା ଦ୍ୱାରା ବିଭିନ୍ନ ଅଞ୍ଚଳର ଲୋକମାନେ ପରସ୍ପର ନିକଟବର୍ତ୍ତୀ ହେଉଛନ୍ତି । ଏହାଦ୍ୱାରା ଭାବର ଆଦାନ ପ୍ରଦାନ ମାଧ୍ୟମରେ ଭେଦଭାବ ଦୂର ହୋଇ ଏକତା ଭାବ ସୁଦୃଢ଼ ହେଉଛି । ରାସ୍ତା ଘାଟର ଉନ୍ନତି ଫଳରେ ପାହାଡ଼, ପର୍ବତ, ଜଙ୍ଗଲ ଓ ଖଣିଖାଦାନରେ ଅବ୍ୟବହୃତ ହୋଇ ପଡ଼ିଥିବା ପ୍ରାକୃତିକ ସମ୍ବଳଗୁଡ଼ିକୁ ଉତ୍ପାଦନ କାର୍ଯ୍ୟରେ ଲଗାଯାଇପାରୁଛି । ପରିବହନ ବ୍ୟବସ୍ଥା ଦ୍ୱାରା ଶିଳ୍ପ କ୍ଷେତ୍ରକୁ କଞ୍ଚାମାଲ, ଜାଳେଣି ଓ ଯନ୍ତ୍ରପାତି ଯୋଗାଇ ହେଉଛି ଏବଂ ଉତ୍ପାଦିତ ଦ୍ରବ୍ୟଗୁଡ଼ିକୁ ବଜାରରେ ପହଞ୍ଚାଇ ଦିଆଯାଇ ପାରୁଛି । ପରିବହନ ବ୍ୟବସ୍ଥା ଯୁଦ୍ଧ, ପ୍ରାକୃତିକ ବିପର୍ଯ୍ୟୟ ଓ ଅନ୍ୟାନ୍ୟ ଆପଦକାଳୀନ ପରିସ୍ଥିତିରେ ସଂଯୋଗସ୍ଥାପନ, ମାଲପରିବହନ ଓ ବଣ୍ଟନରେ ସାହାଯ୍ୟ କରେ ।

ପରିବହନ ତିନୋଟି ଭାବରେ କରାଯାଏ - ସ୍ଥଳ ପରିବହନ, ଜଳ ପରିବହନ ଏବଂ ଆକାଶ ପରିବହନ । ଜଳ, ସ୍ଥଳ ଓ ଆକାଶକୁ ନେଇ ଭାରତରେ ପାଞ୍ଚପ୍ରକାର ପରିବହନ ବ୍ୟବସ୍ଥା କାର୍ଯ୍ୟକାରୀ ହେଉଛି । ସେଗୁଡ଼ିକ ହେଲା -

(i) **ସଡ଼କପଥ** (ii) **ରେଳପଥ**
(iii) **ପାଇପ୍‌ଲାଇନ୍** (iv) **ଜଳପଥ**
(v) **ଆକାଶପଥ**

ସଡ଼କପଥ (Roadways) : ସଡ଼କ ପଥ ସମସ୍ତ ପରିବହନ ବ୍ୟବସ୍ଥା ମଧ୍ୟରେ ଅଧିକ ଗୁରୁତ୍ୱ ପୂର୍ଣ୍ଣ । ଭାରତର

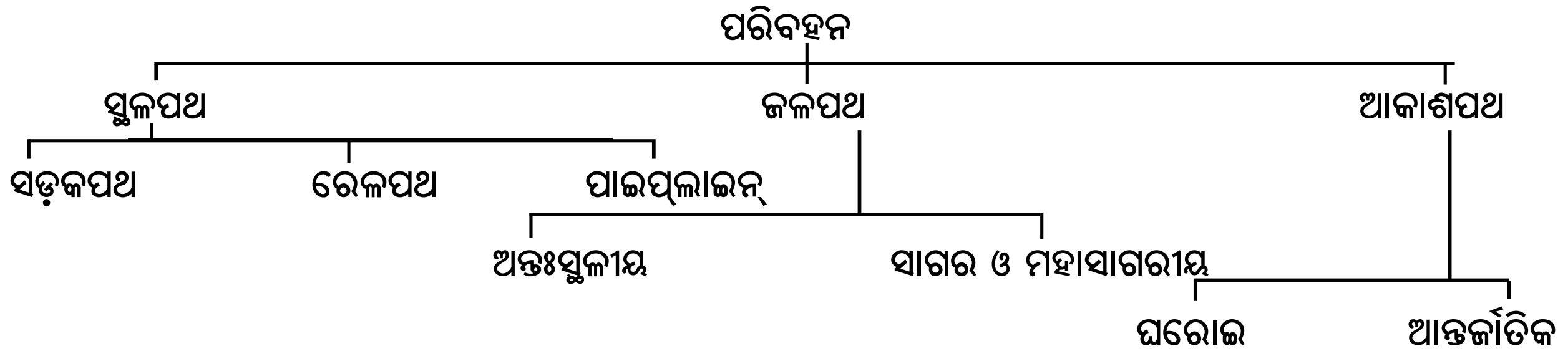

ସଡ଼କପଥ, ପୃଥିବୀର ବୃହତ୍ ପରିବହନ ବ୍ୟବସ୍ଥା ମଧ୍ୟରୁ ଅନ୍ୟତମ । ଆମଦେଶରେ ସଡ଼କ ପଥ ନିର୍ମାଣ ବହୁପୁରାତନ କାଳରୁ ଆରମ୍ଭ ହୋଇଥିଲା । ପ୍ରାଚୀନ ମହେଞ୍ଜୋଦାରୋ ଓ ହରପ୍ପା ସଭ୍ୟତାରୁ ଏହାର ପ୍ରମାଣ ମିଳେ । ଅଶୋକ ଏବଂ ଚନ୍ଦ୍ରଗୁପ୍ତ ମୌର୍ଯ୍ୟଙ୍କ ଭଳି ଶାସକମାନଙ୍କ ଉଦ୍ୟମରେ ଭାରତରେ ସଡ଼କ ପଥ ନିର୍ମାଣ ହୋଇଥିଲା । ମୋଗଲ ରାଜୁତିକାଳରେ ମଧ୍ୟ ଉତ୍ତମ ସଡ଼କ ନିର୍ମାଣ ହୋଇଥିଲା । ଆଜିର ଅନେକ ସଡ଼କ ପଥ ସେହି ମୋଗଲ ଯୁଗର ସଡ଼କ ପଥକୁ ଅନୁସରଣ କରି ନିର୍ମିତ ହୋଇଛି । ଶେରଶାହାଙ୍କ ଅମଳରେ ପୂର୍ବରେ କୋଲକତା ଠାରୁ ଗାଙ୍ଗେୟ ସମତଳ ମଧ୍ୟ ଦେଇ ପଶ୍ଚିମରେ ପେଶୱାର (ଅଧୁନା ପାକିସ୍ଥାନ) ପର୍ଯ୍ୟନ୍ତ ଏକ ସଡ଼କ ପଥ ନିର୍ମାଣ କରାଯାଇଥିଲା । ଏହାକୁ (Grand Trunk Rood) ଗ୍ରାଣ୍ଡଟ୍ରଙ୍କ୍ ରୋଡ୍ କୁହାଯାଏ । ଭାରତର ଆୟତନ ଓ ଜନସଂଖ୍ୟା ତୁଳନାରେ ପରିବହନ ବ୍ୟବସ୍ଥା ସନ୍ତୋଷ ଜନକ ନୁହେଁ । ସଡ଼କପଥ ଦ୍ୱାରା ଅଳ୍ପ ଓ ମଧ୍ୟମ ଦୂରତ୍ୱ ପାଇଁ ଯାତ୍ରୀ ଓ ଜିନିଷପତ୍ର ପରିବହନ ସୁବିଧାଜନକ । ସଡ଼କ ପଥ ନିର୍ମାଣ ଓ ରକ୍ଷଣାବେକ୍ଷଣ ପାଇଁ ରେଳପରିବହନ ତୁଳନାରେ ଖର୍ଚ୍ଚ କମ୍ । ପାର୍ବତ୍ୟାଞ୍ଚଳରେ ମଧ୍ୟ ସଡ଼କ ନିର୍ମାଣ କରାଯାଇପାରେ । ସଡ଼କ ପରିବହନ ଦ୍ୱାରା ଘରକୁ ଘର ସେବା (Door to Door Service) ଯୋଗାଇ ଦିଆଯାଇପାରେ, ଯାହା ରେଳପଥ ପଥ ଦ୍ୱାରା ସମ୍ଭବ ନୁହେଁ । କ୍ଷୟଶୀଳ (Perishable) ବା ଶୀଘ୍ର ପଚିସଢ଼ି ଯାଉଥିବା ଦ୍ରବ୍ୟ ଯଥା: ପନିପରିବା ଓ ଫଳ ଇତ୍ୟାଦିର ପରିବହନ ସଡ଼କ ପଥରେ କରାଯିବା ଅନ୍ୟ ମାଧ୍ୟମଗୁଡ଼ିକ ଠାରୁ ଅଧିକ କାର୍ଯ୍ୟକ୍ଷମ । ବହୁଦୂରକୁ ଯାତ୍ରୀ ଓ ଜିନିଷପତ୍ର ପରିବହନ କରାଯିବା କ୍ଷେତ୍ରରେ ସଡ଼କ ପଥ, ରେଳ ପଥ ତୁଳନାରେ କମ୍ ସୁବିଧା ଜନକ ହୋଇଥାଏ ।

ପ୍ରଥମ ପଞ୍ଚବାର୍ଷିକ ଯୋଜନାର ପ୍ରାରମ୍ଭରୁ ପରିବହନ ବ୍ୟବସ୍ଥାର ବିକାଶ ଉପରେ ଗୁରୁତ୍ୱ ଦିଆଯାଇଥିଲା । ବର୍ତ୍ତମାନ ଭାରତର ସମୁଦାୟ ସଡ଼କ ପଥର ଦୈର୍ଘ୍ୟ ପ୍ରାୟ 59.32 ଲକ୍ଷ କି.ମି. । ଏଥିରେ ଉଭୟ ପକ୍କା ଓ କଚ୍ଚା ରାସ୍ତା ଅନ୍ତର୍ଭୁକ୍ତ । ସଡ଼କ ପଥ ପରିବହନ ବ୍ୟବସ୍ଥାରେ ଭାରତର ସ୍ଥାନ ପୃଥିବୀରେ ଦ୍ୱିତୀୟ ।

ଭାରତରେ ସଡ଼କପଥକୁ ବିଭିନ୍ନ ଶ୍ରେଣୀରେ ବିଭକ୍ତ କରାଯାଇଛି । (i) ଜାତୀୟ ରାଜପଥ (National Highways) (ii) ରାଜ୍ୟ ରାଜପଥ (State Highways) (iii) ମୁଖ୍ୟ ଜିଲ୍ଲା ସଡ଼କପଥ (Major District Roads) (iv) ଗ୍ରାମ୍ୟ ସଡ଼କପଥ (Rural Roads) (v) ସୀମାନ୍ତ ସଡ଼କପଥ (Border Roads) (vi) ସ୍ୱର୍ଣ୍ଣଚତୁର୍ଭୁଜ ରାଜମାର୍ଗ (Golden Quadrilateral Super Highways) (vii) ଆନ୍ତର୍ଜାତୀୟ ରାଜପଥ (International Highways) (viii) ଦ୍ରୁତିତରାଜମାର୍ଗ (Express Highway)

(i) ଜାତୀୟ ରାଜପଥ (National Highways) :

ଜାତୀୟ ରାଜପଥଗୁଡ଼ିକ ରାଜ୍ୟ ଗୁଡ଼ିକର ରାଜଧାନୀ, ପ୍ରଧାନସହର, ଶିଳ୍ପ ଓ ଖଣି ଅଞ୍ଚଳ ଏବଂ ବନ୍ଦରଗୁଡ଼ିକୁ ସଂଯୋଗ କରିଥାଏ । ଏହି ସଡ଼କ ପଥର ନିର୍ମାଣ ଓ ରକ୍ଷାଣବେକ୍ଷଣ କେନ୍ଦ୍ର ସରକାରଙ୍କର କେନ୍ଦ୍ରୀୟ ଲୋକନିର୍ମାଣ ବିଭାଗ (Central Public Works Depatment -CPWD) ଉପରେ ନ୍ୟସ୍ତଥାଏ । ଆମ ଦେଶରେ ପ୍ରାୟ 1 ଲକ୍ଷ 42 ହଜାର କି.ମି. ଦୈର୍ଘ୍ୟର ଜାତୀୟ ରାଜପଥ ଅଛି । ଏହି ପଥ ଦେଇ ଦେଶର ଶତକଡ଼ା ପ୍ରାୟ 40 ଭାଗ ଯାତ୍ରୀ ଓ ମାଲ ପରିବହନ ହୋଇଥାଏ । 16 ନମ୍ବର ଜାତୀୟ ରାଜପଥ କୋଲକାତାରୁ ବାହାରି ଆମ ରାଜ୍ୟର ରାଜଧାନୀ ଭୁବନେଶ୍ୱର ଦେଇ ଚେନ୍ନାଇ ପଯ୍ୟନ୍ତ ଯାଇଛି ।

କୋଲକାତାରୁ ବାହାରି ଆସାନସୋଲ, କାନପୁର, ଦିଲ୍ଲୀ ଆଦି ସହର ଦେଇ ଅମୃତସର ପର୍ଯ୍ୟନ୍ତ ଯାଇଥିବା ଗ୍ରାଣ୍ଡଟ୍ରଙ୍କ ରୋଡ଼ (Grand Trunk Road) ଦେଶର ସର୍ବ ପୁରାତନ ଜାତୀୟ ରାଜପଥ ।

ଭାରତର ଦୀର୍ଘତମ ଜାତୀୟ ରାଜପଥ **NH-44** ଶ୍ରୀନଗର ଠାରୁ କନ୍ୟାକୁମାରୀ ପର୍ଯ୍ୟନ୍ତ ଯାଇଅଛି । ଏହା 3745 କି.ମି. ଦୈର୍ଘ୍ୟ ବିଶିଷ୍ଟ। (ଚିତ୍ର : 20 ଦେଖ)

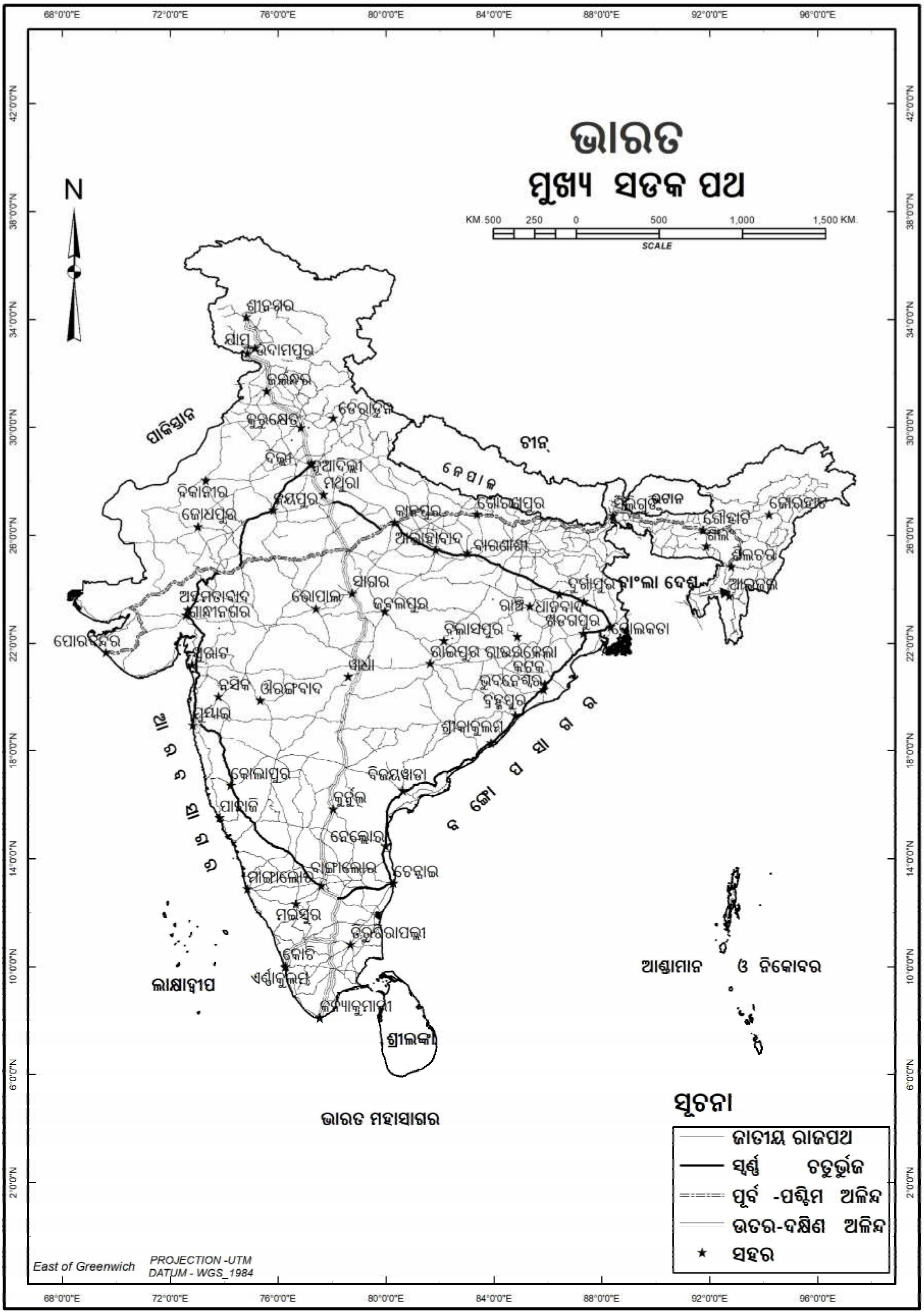
ଭାରତ
ମୁଖ୍ୟ ସଡକ ପଥ
N
KM 500 250 0 500 1,000 1,500 KM.
SCALE
ପାକିସ୍ତାନ
ଚୀନ୍
ନେପାଳ
ଭୁଟାନ
ବାଂଲା ଦେଶ
ଶ୍ରୀନଗର
ଜାମ୍ମୁ
ଜଳନ୍ଧର
କୁରୁକ୍ଷେତ୍ର
ଡେରାଡୁନ
ଦିଲ୍ଲୀ
ମଥୁରା
ବିକାନୀର
ଜୟପୁର
ଯୋଧପୁର
କାନପୁର
ଗୋରଖପୁର
ଆଲାହାବାଦ
ବାରଣାଶୀ
ଗୌହାଟି
ଶିଲଚର
ଅହମଦାବାଦ
ଗାନ୍ଧୀନଗର
ଭୋପାଳ
ସାଗର
ଜବଲପୁର
ରାଞ୍ଚି
ଧାନବାଦ
ଦୁର୍ଗାପୁର
ଖଡଗପୁର
କୋଲକତା
ପୋରବନ୍ଦର
ସୁରାଟ
ବିଲାସପୁର
ରାଉରକେଲା
ରାଇପୁର
କଟକ
ଭୁବନେଶ୍ୱର
ବ୍ରହ୍ମପୁର
ନାସିକ
ଔରଙ୍ଗବାଦ
ମୁମ୍ବାଇ
ଶ୍ରୀକାକୁଲମ
ଆରବ ସାଗର
ବଙ୍ଗୋପସାଗର
କୋଲାପୁର
ବିଜୟୱାଡା
କର୍ଣ୍ଣୁଲ
ନେଲ୍ଲୋର
ମାଙ୍ଗାଲୋର
ବାଙ୍ଗାଲୋର
ଚେନ୍ନାଇ
ମହୀସୁର
ତିରୁଚିରାପଲ୍ଲୀ
କୋଚି
ଏର୍ଣ୍ଣାକୁଲମ
କନ୍ୟାକୁମାରୀ
ଲାକ୍ଷାଦ୍ୱୀପ
ଶ୍ରୀଲଙ୍କା
ଆଣ୍ଡାମାନ ଓ ନିକୋବର
ଭାରତ ମହାସାଗର
ସୂଚନା
ଜାତୀୟ ରାଜପଥ
ସ୍ୱର୍ଣ୍ଣ ଚତୁର୍ଭୁଜ
ପୂର୍ବ -ପଶ୍ଚିମ ଅଳିନ୍ଦ
ଉତର-ଦକ୍ଷିଣ ଅଳିନ୍ଦ
ସହର
East of Greenwich
PROJECTION -UTM
DATUM - WGS_1984

ଚିତ୍ର : 20

(ii) ରାଜ୍ୟ ରାଜପଥ (State Highways - SH) :

ରାଜ୍ୟ ରାଜପଥ ଗୁଡ଼ିକର ନିର୍ମାଣ ଓ ରକ୍ଷଣା ବେକ୍ଷଣ ରାଜ୍ୟ ସରକାରଙ୍କର (Public works Department- PWD) କରିଥାନ୍ତି । ରାଜ୍ୟର ରାଜଧାନୀକୁ ବିଭିନ୍ନ ଜିଲ୍ଲାର ସଦର ମହକୁମା, ପ୍ରଧାନ ସହର ଓ ଶିଳ୍ପ କେନ୍ଦ୍ରଗୁଡ଼ିକୁ ସଂଯୋଗ କରିଥାଏ । ଦେଶରେ ପ୍ରାୟ 1.7 ଲକ୍ଷ କିଲୋମିଟର ଦୈର୍ଘ୍ୟ ରାଜ୍ୟ ରାଜପଥ ଅଛି । ମହାରାଷ୍ଟ୍ରରେ ରାଜ୍ୟ ରାଜପଥର ପରିମାଣ ସବୁଠାରୁ ଅଧିକ । ଏହା ପ୍ରାୟ 33705 କିଲୋମିଟର । ଏହା ପଛକୁ କର୍ଣ୍ଣାଟକ ରାଜ୍ୟ ରାଜପଥର ଦୈର୍ଘ୍ୟ ପ୍ରାୟ 20738 କିଲୋମିଟର ।

(iii) ଜିଲ୍ଲା ସଡ଼କପଥ (Major District Roads) : ମୁଖ୍ୟ ଜିଲ୍ଲାସଡ଼କଗୁଡ଼ିକ ସଂପୃକ୍ତ ଜିଲ୍ଲାର ସଦର ମହକୁମାକୁ ଏହାର ପ୍ରଧାନ ସହର ବ୍ଲକ, ତହସିଲ ଓ ବଡ଼ ବଡ଼ ଗ୍ରାମ ସହିତ ସଂଯୁକ୍ତ କରିଥାଏ । ବର୍ତ୍ତମାନ ଏହାର ରକ୍ଷାଣବେକ୍ଷଣ ଦାୟିତ୍ୱ ଜିଲ୍ଲାପରିଷଦକୁ ଦିଆଯାଇଛି । ଦେଶରେ ପ୍ରାୟ 6,03,292 କିଲୋମିଟର ଦୈର୍ଘ୍ୟ ଜିଲ୍ଲା ସଡ଼କପଥ ରହିଛି ।

(iv) ଗ୍ରାମ୍ୟ ସଡ଼କ (Rural Roads) :

ଗ୍ରାମ୍ୟ ସଡ଼କଗୁଡ଼ିକ ନିକଟବର୍ତ୍ତୀ ସହର ଓ ବଜାରଗୁଡ଼ିକୁ ସଂଯୋଗ କରିଥାଏ । ଏହାକୁ ବର୍ତ୍ତମାନ ପ୍ରଧାନମନ୍ତ୍ରୀଗ୍ରାମ୍ୟ ସଡ଼କ ଯୋଜନାର ଅନ୍ତର୍ଭୁକ୍ତ କରାଯାଇଛି । ପ୍ରଧାନମନ୍ତ୍ରୀ ଗ୍ରାମ୍ୟ ସଡ଼କ ନିର୍ମାଣ ଅଧୀନରେ 5000 ଜନ ସଂଖ୍ୟା ବିଶିଷ୍ଟ ଗ୍ରାମଗୁଡ଼ିକୁ ତାର ପ୍ରଧାନ ସହର ସହିତ କଂକ୍ରିଟ୍ ରାସ୍ତା ଦ୍ୱାରା ସଂଯୁକ୍ତ କରାଯାଇଛି । ଓଡ଼ିଶାର ଗ୍ରାମ୍ୟ ସଡ଼କ ପଥର ଦୈର୍ଘ୍ୟ ପ୍ରାୟ 26 ଲକ୍ଷ କି.ମି. ।

(v) ସ୍ୱର୍ଣ୍ଣ ଚତୁର୍ଭୁଜ ମହାରାଜମାର୍ଗ :- (Golden Quodrilateral Super Highways)

ଏହା ଦ୍ୱାରା ଦିଲ୍ଲୀ, କୋଲକାତା, ଚେନ୍ନାଇ ଓ ମୁମ୍ବାଇ ସହରଗୁଡ଼ିକୁ ପରସ୍ପର ସହିତ ସଂଯୁକ୍ତ କରାଯାଇଛି । ଏହାର ଦୈର୍ଘ୍ୟ ପ୍ରାୟ 5840 କିଲୋମିଟର ରହିଛି ।

ଉତ୍ତର-ଦକ୍ଷିଣ ଓ ପୂର୍ବ-ପଶ୍ଚିମ ଅଳିନ୍ଦ (N-S & E-W Corridor) : ଉତ୍ତରରେ ଜାମ୍ମୁକାଶ୍ମୀରର ଶ୍ରୀନଗରକୁ ଦକ୍ଷିଣରେ ତାମିଲନାଡୁର କନ୍ୟାକୁମାରୀ ପର୍ଯ୍ୟନ୍ତ ଓ ପଶ୍ଚିମରେ ଗୁଜରାଟର ପୋରବନ୍ଦରଠାରୁ ପୂର୍ବରେ ଆସାମର ସିଲ୍‌ଚର ପର୍ଯ୍ୟନ୍ତ 4 ରୁ 6 ଲେନ୍ ବିଶିଷ୍ଟ ରାସ୍ତା ଉତ୍ତର-ଦକ୍ଷିଣ ଓ ପୂର୍ବ-ପଶ୍ଚିମ ଅଳିନ୍ଦ ନାମରେ ନିର୍ମାଣ କରାଯାଇଛି ।ଏହି ଦୁଇଟିର ଦୈର୍ଘ୍ୟ ପ୍ରାୟ 7300 କିଲୋମିଟର ।ସ୍ୱର୍ଣ୍ଣ ଚତୁର୍ଭୁଜ ଏବଂ ଉତ୍ତର-ଦକ୍ଷିଣ ଓ ପୂର୍ବପଶ୍ଚିମ (କରିଡ଼ର) ଅଳିନ୍ଦ ସହିତ ଦେଶର 10ଟି ପ୍ରଧାନ ବନ୍ଦର ଗୁଡ଼ିକୁ ସଂଯୁକ୍ତ କରାଯାଇଛି । ଏହି ବନ୍ଦରଗୁଡ଼ିକ ହେଲା କାଣ୍ଡଲା, ମାର୍ମାଗାଓ, ମାଙ୍ଗାଲୋର, କୋଚି, ତୁତିକୋରିନ, ଚେନ୍ନାଇ,ଏନୋର, (ତାମିଲନାଡୁ) ବିଶାଖାପାଟଣା, ପାରାଦ୍ୱୀପ ଏବଂ ହଳଦିଆ ।

ଏହି ସ୍ୱର୍ଣ୍ଣ ଚତୁର୍ଭୁଜ ମହାରାଜମାର୍ଗ ଦ୍ୱାରା ଦେଶର ଦିଲ୍ଲୀ-କୋଲକାତା-ଚେନ୍ନାଇ-ମୁମ୍ବାଇର ଗମନାଗମନ ଓ ପରିବହନ ପାଇଁ ସମୟ ଓ ଦୂରତା ହ୍ରାସ ପାଇଛି ।

ସୀମାନ୍ତ ସଡ଼କ ପଥ (Border Roads Organisation) : 1960 ମସିହା ପରଠାରୁ ସୀମାନ୍ତ ସଡ଼କ ସଂସ୍ଥା (Border Roads Organisation) ପ୍ରତିଷ୍ଠା କରାଯାଇଛି । ଜାତୀୟ ସୁରକ୍ଷାକୁ ସୁଦୃଢ଼ କରିବା ପାଇଁ ସୀମାନ୍ତବର୍ତ୍ତୀ ଅଞ୍ଚଳରେ ରାସ୍ତା ନିର୍ମାଣ କରାଯାଇଛି । ସୀମାନ୍ତ ସଡ଼କ ମଧ୍ୟରେ ଏହି ସଂସ୍ଥା ଦ୍ୱାରା ନିର୍ମିତ ହିମାଚଳ ପ୍ରଦେଶର ମନାଲି ଠାରୁ ଲାଦାଖର ସଦର ମହକୁମା ଲେହ ପର୍ଯ୍ୟନ୍ତ ଯାଇଥିବା ରାସ୍ତା ପୃଥିବୀର ସର୍ବୋଚ୍ଚ ସଡ଼କ ପଥ । ମାତ୍ର ଦେଶର ସୁରକ୍ଷା ଦୃଷ୍ଟିକୋଣରୁ ରାଜଧାନୀ ଦିଲ୍ଲୀରୁ ଚଣ୍ଡୀଗଡ଼କୁ ସଂଯୁକ୍ତ କରି ଭାରତ ଓ ଚୀନ ସୀମାନ୍ତବର୍ତ୍ତୀ ସିପକିଲ୍ଲା ଗିରିପଥ ଦେଇ ଶିମଳା ର ଉତ୍ତର ପଟେ ଏକ ରାଜମାର୍ଗ ନିର୍ମିତ ହୋଇଛି । ଅତ୍ୟନ୍ତ ବିପଦ ଶଂକୁଳ ପାର୍ବତ୍ୟାଞ୍ଚଳ, ଘଞ୍ଚଅରଣ୍ୟ, ଅସହ୍ୟ ପ୍ରତିକୂଳ ପରିସ୍ଥିତିରେ ଅସ୍ୱାସ୍ଥ୍ୟକର ଅଞ୍ଚଳରେ ସୀମାନ୍ତସଡ଼କ ସଂସ୍ଥା ଏହିସବୁ ସୀମାନ୍ତ ସଡ଼କ ନିର୍ମାଣ କରାଇଛି ।

ଦ୍ରୁତ ରାଜମାର୍ଗ (Express Highway) :

ଦ୍ରୁତ ଗାଡ଼ିଚାଳନା ପାଇଁ ନିର୍ମିତ ଉଚ୍ଚମାନର 6-8 ଲେନ୍ ବିଶିଷ୍ଟ ରାସ୍ତାଗୁଡ଼ିକୁ ଏକ୍ସପ୍ରେସ୍ ହାଇୱେ ବା ଦ୍ରୁତ ରାଜମାର୍ଗ କୁହାଯାଏ । ଏହି ସଡ଼କଗୁଡ଼ିକ ଅତ୍ୟନ୍ତ ଉଚ୍ଚମାନର ଏବଂ 12 ଲେନ୍ ବିଶିଷ୍ଟ ହେବା ପାଇଁ ବ୍ୟବସ୍ଥା କରାଯାଇଛି ।

ଭାରତରେ ନିର୍ମାଣ କରାଯାଇଥିବା ଏକ୍ସପ୍ରେସ୍ ହାଇୱେର ଦୈର୍ଘ୍ୟ ପ୍ରାୟ 1652 କି.ମି.(2020)।ସେଗୁଡ଼ିକ ହେଲା ଆଗ୍ରା-ଲକ୍ଷ୍ନୌ ଦ୍ରୁତ ରାଜମାର୍ଗ, ଦିଲ୍ଲୀ-ମିରଟ୍ ଦ୍ରୁତ ରାଜମାର୍ଗ, ମୁମ୍ବାଇ-ପୁଣେ ଦ୍ରୁତ ରାଜମାର୍ଗ, କୋଲକାତା - ଦମଦମ୍

ବିମାନବନ୍ଦର ଦ୍ରୁତ ରାଜମାର୍ଗ ଚଣ୍ଡୀଖୋଲ - ସୁକିନ୍ଦା ଦ୍ରୁତ ରାଜମାର୍ଗ, କୋଲକାତା-ଦୁର୍ଗାପୁର ଦ୍ରୁତ ରାଜମାର୍ଗ ଏବଂ ଦିଲ୍ଲୀ-ଆଗ୍ରା ଦ୍ରୁତ ରାଜମାର୍ଗ । ବର୍ତ୍ତମାନ ଦିଲ୍ଲୀ ଠାରୁ ମୁମ୍ବାଇ ପର୍ଯ୍ୟନ୍ତ 1350 କି.ମି. ଏକ୍ସପ୍ରେସ୍ ହାଇୱେ କାମ କରାଯାଉଛି ।

ଆନ୍ତର୍ଜାତୀୟ ରାଜମାର୍ଗ (International Highway)

ଦେଶରେ ଦ୍ରୁତଗାମୀ ଯାନବାହନର ସଂଖ୍ୟା ବୃଦ୍ଧି ଏବଂ ଯାତ୍ରୀ ଓ ମାଲ ସରବରାହକୁ ଆଖି ଆଗରେ ରଖି ଆନ୍ତର୍ଜାତୀୟ ରାଜମାର୍ଗ ନିର୍ମାଣ କରାଯାଇଛି । ଏହା ବିଶ୍ୱବ୍ୟାଙ୍କର ସହାୟତାରେ ନିର୍ମିତ ହେଉଛି । ଏହାଦ୍ୱାରା ଭାରତର ସଡ଼କଗୁଡ଼ିକ ପଡ଼ୋଶୀ ଦେଶର ରାସ୍ତା ସହିତ ସଂଯୋଗ କରାଯାଇପାରିଛି । ଉକ୍ତ ଦେଶଗୁଡ଼ିକ ହେଲା - ପାକିସ୍ଥାନ, ନେପାଳ, ଭୁଟାନ, ବଙ୍ଗଳାଦେଶ ଓ ମ୍ୟାଆଁମାର ।

ରେଳପଥ (Railways) :- ରେଳପଥ ଦୂରସ୍ଥାନକୁ ସ୍ଥଳ ପଥରେ ଯାତ୍ରୀ ଓ ମାଲ ପରିବହନର ମୁଖ୍ୟ ମାଧ୍ୟମ । ଆମ ଦେଶରେ 1853 ମସିହାରେ ରେଳଚଳାଚଳର ଶୁଭାରମ୍ଭ ହୋଇଥିଲା । ସେହି ବର୍ଷ ଏପ୍ରିଲ ମାସରେ ବମ୍ବେରୁ ଥାଣେ ପର୍ଯ୍ୟନ୍ତ 34 କି.ମି. ଦୈର୍ଘ୍ୟ ବିଶିଷ୍ଟ ରେଳଧାରଣା ଉପରେ ପ୍ରଥମଥର ପାଇଁ ରେଳଗାଡ଼ି ଚାଲିଥିଲା । ସେହି 1854ରେ ଅନ୍ୟ ଦୁଇଟି ରେଳପଥ କୋଲକାତା ଓ ରାଣୀଗଞ୍ଜ ମଧ୍ୟରେ ଏବଂ 1856ରେ ଚେନ୍ନାଇ ଓ ଆରକୋନାମ ମଧ୍ୟରେ ଚାଲିଥିଲା । ତେଣୁ ଭାରତୀୟ ରେଳବାଇ 150 ବର୍ଷରୁ ଅଧିକ ସମୟ ଧରି ଦେଶର ରେଳସେବା ପ୍ରଦାନ କରିଆସୁଛି । ଭାରତୀୟ ରେଳ ପଥର ସ୍ଥାନ ଏସିଆ ମହାଦେଶରେ ଦ୍ୱିତୀୟ ଏବଂ ପୃଥିବୀରେ ତୃତୀୟ । (ଯୁକ୍ତରାଷ୍ଟ୍ର ଆମେରିକା ପ୍ରଥମ-224,792 କି.ମି. ଏବଂ ଚୀନ ଦ୍ୱିତୀୟ- 98,000କି.ମି.) ଭାରତୀୟ ରେଳପଥର ମୋଟ ଦୈର୍ଘ୍ୟ ପ୍ରାୟ 67368 କି.ମି. । ଏଥି ମଧ୍ୟରେ ପ୍ରାୟ 22224 କି.ମି. (ବିଦ୍ୟୁତୀକରଣ) ହୋଇଛି । ଏହା ଭାରତର ବୃହତ୍ତମ ରାଷ୍ଟ୍ରାୟତ୍ତ ସଂସ୍ଥା, ଯେଉଁଥିରେ ସର୍ବାଧିକ କର୍ମଚାରୀ କାମ କରନ୍ତି । ପ୍ରାୟ 1800 ଟ୍ରେନ ଦ୍ୱାରା ପ୍ରତିଦିନ ପ୍ରାୟ ଦୁଇ କୋଟି ଯାତ୍ରୀ ଯାତାୟତ କରିଥାନ୍ତି । ରେଳପଥ ଦ୍ୱାରା ପ୍ରାୟ 100 ଶତାଂଶ ଲୁହାପଥର, ଲୁହା ଓ ଇସ୍ପାତ, 98 ଶତାଂଶ ଖଣିଜ ତୈଳ, 98 ଶତାଂଶ ମାଙ୍ଗାନିଜ, 98 ଶତାଂଶ ଗୃହନିର୍ମାଣ ପଥର, 90 ଶତାଂଶ ସିମେଣ୍ଟ, 90 ଶତାଂଶ କଞ୍ଚା କାର୍ପାସ, 90 ଶତାଂଶ ଧାତବ ପଥର, 65 ଶତାଂଶ କାର୍ପାସ ବୟନ ବସ୍ତୁ, 50 ଶତାଂଶ ସାର, ଏବଂ 35 ଶତାଂଶ ଖାଦ୍ୟଶସ୍ୟ ପରିବହନ ହୋଇଥାଏ । ଦେଶରେ ରେଳ ପରିବହନର ଗୁରୁତ୍ୱ ଦୃଷ୍ଟିରୁ ଯୋଜନାବଦ୍ଧ ଭାବରେ ରେଳ ବ୍ୟବସ୍ଥାର ଉନ୍ନତି ଉପରେ ବିଶେଷ ଧ୍ୟାନ ଦିଆଯାଉଛି । ଏବେ ମଧ୍ୟ ବିଭିନ୍ନ ଗେଜର ରେଳପଥ ଆମଦେଶରେ କାର୍ଯ୍ୟକାରୀ ହେଉଅଛି । ଏଗୁଡ଼ିକ ହେଲା **ବ୍ରଡ଼ଗେଜ୍** (ଦୁଇରେଳ ଧାରଣା ମଧ୍ୟରେ ବ୍ୟବଧାନ 1.676 ମିଟର ।) **ମିଟର ଗେଜ୍** (ଦୁଇରେଳ ଧାରଣା ମଧ୍ୟରେ ବ୍ୟବଧାନ 1 ମିଟର) **ନାରୋ ଗେଜ** (ଦୁଇ ରେଳ ଧାରଣା ମଧ୍ୟରେ ବ୍ୟବଧାନ 0.762 ମିଟର ଏବଂ **ଲିଫଟ ଗେଜ** ବା **ଲାଇଟ ଗେଜ** (ଦୁଇ ରେଳଧାରଣା ମଧ୍ୟରେ ବ୍ୟବଧାନ 0.610 ମିଟର) । ଯାତ୍ରୀ ଓ ମାଲପରିବହନ ଅତିମାତ୍ରାରେ ବଢ଼ିଚାଲିଛି । ଗୋଟିଏ ଗେଜ୍ ଟ୍ରେନ୍‌ରୁ ଅନ୍ୟ ଗୋଟିଏ ଟ୍ରେନ୍‌କୁ ମାଲ ସ୍ଥାନାନ୍ତରଣ କରିବାକୁ ଖର୍ଚ୍ଚ ଅଧିକ ପଡୁଛି । ଏତଦ୍‌ବ୍ୟତୀତ ଦ୍ରୁତ ରପ୍ତାନି କ୍ଷେତ୍ରରେ ଦୁର୍ଭିକ୍ଷ, ପ୍ରାକୃତିକ ବିପର୍ଯ୍ୟୟ ଏବଂ ସୈନ୍ୟ ପରିଚାଳନା ସମୟରେ ସମୟର ଅପଚୟ ଘଟିଥାଏ । ତେଣୁ ଅଗ୍ରାଧିକାର ଭିତ୍ତିରେ ନାରୋଗେଜ୍ ଓ ମିଟର ଗେଜ୍ ଲାଇନ୍ ଗୁଡ଼ିକୁ ବ୍ରଡ଼ଗେଜରେ ପରିଣତ କରାଯାଉଛି । ବାଷ୍ପଚାଳିତ ଇଂଜିନ ସ୍ଥାନରେ ଡିଜେଲ କିମ୍ବା ବିଦ୍ୟୁତିକ ରେଳ ଇଞ୍ଜିନ କାର୍ଯ୍ୟରେ ଲଗାଯାଉଛି । ଏହା ଦ୍ୱାରା କାର୍ଯ୍ୟ ଦକ୍ଷତା ବୃଦ୍ଧି ପାଉଛି ଏବଂ ପ୍ରଦୂଷଣ ହ୍ରାସ ପାଉଛି । ରେଳପଥ ବିଦ୍ୟୁତକରଣ କାର୍ଯ୍ୟକ୍ରମକୁ ଅଗ୍ରାଧିକାର ଦିଆଯାଉଛି । ଦୁର୍ଘଟଣା ରୋକିବା ପାଇଁ ଅତ୍ୟାଧୁନିକ ସିଗନାଲ ବ୍ୟବସ୍ଥା ପ୍ରଚଳନ କରାଯାଉଛି । ଶୀତତାପ ନିୟନ୍ତ୍ରିତ ଯାତ୍ରୀବାହୀ ବଗି ବ୍ୟବହାର, ଦ୍ରୁତଗାମୀ ଟ୍ରେନ୍ (ରାଜଧାନୀ, ଶତାବ୍ଦୀ) ଇତ୍ୟାଦି ଓ ଇଣ୍ଟର ସିଟି ଦ୍ରୁତଗାମୀ ଟ୍ରେନ୍ ପ୍ରଚଳନ କରାଯାଉଛି । ସ୍ଥାନ ଆରକ୍ଷଣ କମ୍ପ୍ୟୁଟରୀକରଣ କରାଯାଇଛି । ଯାତ୍ରା ସମୟରେ ଯାତ୍ରୀମାନଙ୍କର ଖାଇବା ପିଇବା ବ୍ୟବସ୍ଥା ମଧ୍ୟ ରେଳବାଇ ଦ୍ୱାରା କରାଯାଇଛି । ସ୍ୱାଧୀନତା ପରେ ରେଳ ବିଭାଗକୁ ଜାତୀୟ କରଣ କରାଯାଇ ଏହାର ପରିଚାଳନା ଦାୟିତ୍ୱ ରେଳବାଇ ବୋର୍ଡ଼ (Railway Board) ଉପରେ ନ୍ୟସ୍ତ କରାଯାଇଛି । ପରିଚାଳନାଗତ ସୁବିଧା ପାଇଁ ଦେଶର ସମସ୍ତ ରେଳପଥକୁ ସତରଗୋଟି ମଣ୍ଡଳରେ ବିଭକ୍ତ କରାଯାଇଛି । 2019 ମସିହାରେ ଆନ୍ଧ୍ରପ୍ରଦେଶର ବିଶାଖାପାଟଣାଠାରେ 18 ତମ ରେଳବାଇ ବୋର୍ଡ଼ (ଦକ୍ଷିଣ ଉପକୂଳ ରେଳପଥ) ସ୍ଥାପନା ପାଇଁ ଘୋଷଣା କରାଯାଇଛି । ରେଳପଥ ଗୁଡ଼ିକର ନାମ ଓ ତାହାର ମୁଖ୍ୟ କାର୍ଯ୍ୟାଳୟର ନାମ ସାରଣୀ 18ରେ ଦିଆଯାଇଛି । (ଚିତ୍ର : 21 ଦେଖ)

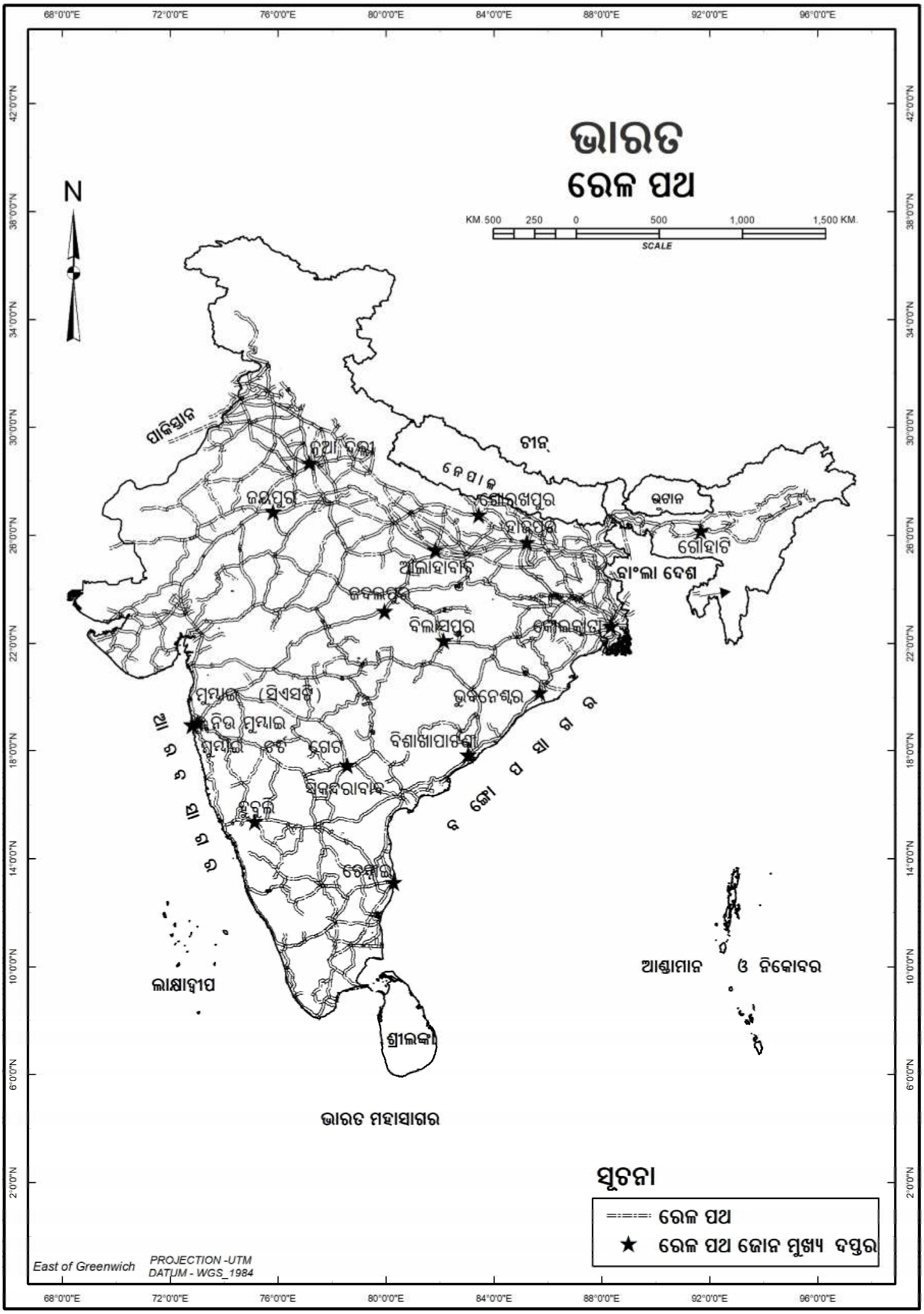

ଭାରତ
ରେଳ ପଥ
KM 500 250 0 500 1,000 1,500 KM.
SCALE
N
ପାକିସ୍ତାନ
ନୂଆଦିଲ୍ଲୀ
ଚୀନ୍
ନେପାଳ
ଜୟପୁର
ଗୋରଖପୁର
ହାଜିପୁର
ଭୁଟାନ
ଗୌହାଟି
ଆଲାହାବାଦ
ବାଂଲା ଦେଶ
ଜବଲପୁର
ବିଲାସପୁର
କୋଲକାତା
ମୁମ୍ବାଇ (ସିଏସଟି)
ଭୁବନେଶ୍ୱର
ନିଉ ମୁମ୍ବାଇ
ବିଶାଖାପାଟଣା
ସିକନ୍ଦରାବାଦ
ହୁବଲି
ଚେନ୍ନାଇ
ଆରବ ସାଗର
ବଙ୍ଗୋପସାଗର
ଲାକ୍ଷାଦ୍ୱୀପ
ଆଣ୍ଡାମାନ ଓ ନିକୋବର
ଶ୍ରୀଲଙ୍କା
ଭାରତ ମହାସାଗର
ସୂଚନା
ରେଳ ପଥ
ରେଳ ପଥ ଜୋନ ମୁଖ୍ୟ ଦପ୍ତର
East of Greenwich
PROJECTION -UTM
DATUM - WGS_1984

ଚିତ୍ର : 21

ସାରଣୀ - 18

ଭାରତର ରେଳପଥ ମଣ୍ଡଳ

କ୍ର.ନ.	ରେଳପଥ ମଣ୍ଡଳ	ମୁଖ୍ୟ କାର୍ଯ୍ୟାଳୟ	ସମୁଦାୟ ଦୈର୍ଘ୍ୟ (କି.ମି.)
1.	ଉତ୍ତର ରେଳପଥ	ନିଉଦିଲ୍ଲୀ	6968
2.	ଦକ୍ଷିଣ ରେଳପଥ	ଚେନ୍ନାଇ	5098
3.	ପୂର୍ବ ରେଳପଥ	କୋଲକାତା (ହାଓ୍ୱଡ଼ା)	2914
4.	ପଶ୍ଚିମ ରେଳପଥ	ମୁମ୍ବାଇ (ଚର୍ଚ୍ଚଗେଟ୍)	6951
5.	କେନ୍ଦ୍ର ରେଳପଥ	ମୁମ୍ବାଇ (CST)	3905
6.	ଦ-ପୂ. ରେଳପଥ	କୋଲକତା	2631
7.	ଉ-ପୂ. ରେଳପଥ	ଗୋରଖପୁର	3667
8.	ଉ-ପୂ. ସୀମାନ୍ତ ରେଳପଥ	ସାଲଇଗାଓ (ଗୁଆହାଟି)	3907
9.	ଦକ୍ଷିଣ-କେନ୍ଦ୍ର ରେଳପଥ	ସିକନ୍ଦରାବାଦ	5952
10.	ପୂର୍ବ-ଉପକୂଳ ରେଳପଥ	ଭୁବନେଶ୍ୱର	2677
11.	ଦକ୍ଷିଣ-ପଶ୍ଚିମ ରେଳପଥ	ହୁବ୍ଲି	3177
12.	ପଶ୍ଚିମ-କେନ୍ଦ୍ର ରେଳପଥ	ଜବଲପୁର	2965
13.	ଉତ୍ତର-କେନ୍ଦ୍ର ରେଳପଥ	ଆଲାହାବାଦ	3151
14.	ଦ-ପୂ-କେନ୍ଦ୍ର ରେଳପଥ	ବିଳାସପୁର	2447
15.	ଉତ୍ତର-ପଶ୍ଚିମ ରେଳପଥ	ଜୟପୁର	5459
16.	ପୂର୍ବକେନ୍ଦ୍ର ରେଳପଥ	ହାଜିପୁର	3628
17.	କଙ୍କଣ ରେଳପଥ	ନିଉମୁମ୍ବାଇ	741
18.	ଦକ୍ଷିଣ-ଉପକୂଳ ରେଳପଥ	ୱାଲଟିଅର (ବିଶାଖାପାଟଣା)	(Announced)

ଭାରତୀୟ ରେଳପଥରେ ଅନେକ ଦ୍ରୁତଗାମୀ ଟ୍ରେନ୍ ଚଳାଚଳ କରୁଛି । ତନ୍ମଧ୍ୟରୁ ହମ୍‌ସଫର ଟ୍ରେନ୍, ରାଜଧାନୀ ଟ୍ରେନ୍, ଶତାବ୍ଦୀ ଟ୍ରେନ୍, ଅନ୍ତୋଦୟ ଟ୍ରେନ୍, ଯୁଦ୍ଧ ଟ୍ରେନ୍, ବନ୍ଦେ ଭାରତ ଟ୍ରେନ୍, ତେଜସ ଟ୍ରେନ୍, ଗତିମାନ ଟ୍ରେନ୍, ସଂପର୍କ କ୍ରାନ୍ତି ଟ୍ରେନ୍, ଡବଲ ଡେକର ଟ୍ରେନ୍ ପ୍ରଭୃତି ଉଲ୍ଲେଖ ଯୋଗ୍ୟ । ଏହା ବ୍ୟତୀତ କେତେକ ଅଞ୍ଚଳରେ ତୀର୍ଥଯାତ୍ରୀ ଟ୍ରେନ୍ ମଧ୍ୟ ଚଳାଚଳ କରୁଛି ।

ଭାରତର ଦୀର୍ଘତମ ରେଳ ଚଳାଚଳ ହେଉଛି ଡ୍ରିବୁଗଡ଼ରୁ କନ୍ୟାକୁମାରୀ, ଏହାର ଦୈର୍ଘ୍ୟ 4286 କିଲୋମିଟର । ଭାରତର ଦୀର୍ଘତମ ରେଳ ଷ୍ଟେସନ ଉତ୍ତର ପ୍ରଦେଶର ଗୋରଖପୁର, ଏହାର ଦୈର୍ଘ୍ୟ 1366.33 ମିଟର । ଭାରତରେ ଥିବା ବିଦ୍ୟୁତ ସଂଯୋଗ ରେଳଲାଇନ୍ ମଧ୍ୟରେ ସବୁଠାରୁ ଦୀର୍ଘତମ ରେଳ ଲାଇନ୍ ଦିଲ୍ଲୀଠାରୁ କୋଲକାତା ପର୍ଯ୍ୟନ୍ତ ଭାୟା ପାଟନା ହୋଇ ଯାଇଛି । ଭାରତରେ ଚାଲୁଥିବା ଟ୍ରେନ୍ ମଧ୍ୟରେ 'ବନ୍ଦେ ଭାରତ - 18' ସବୁଠାରୁ ଦ୍ରୁତଗାମୀ ଟ୍ରେନ୍, ଏହାର ଗତି ଘଣ୍ଟା ପ୍ରତି 180 କି.ମି. ରୁ 200 କି.ମି. ।

ମେଟ୍ରୋଟ୍ରେନ୍ :

ଭାରତରେ ଦ୍ରୁତ ସହରୀକରଣ ହେଉଛି । 2011 ଜନସଂଖ୍ୟା ଗଣନା ଅନୁସାରେ ସହରରେ ପ୍ରାୟ 31 ଶତାଂଶରୁ ଊର୍ଦ୍ଧ୍ୱ ଲୋକ ବାସ କରନ୍ତି । ଅନୁମାନ କରାଯାଉଛି 2031 ରେ ଏହା ବୃଦ୍ଧି ପାଇ 40 ଶତାଂଶ ଓ 2051ରେ 50 ଶତାଂଶ ହେବ । ଦେଶର ସମୁଦାୟ ଘରୋଇ ଉତ୍ପାଦନ GDPର 65 ଶତାଂଶ ବର୍ତ୍ତମାନ ସହରରୁ ମିଳୁଛି, ଯାହାକି 2030ରେ ପ୍ରାୟ 75 ଶତାଂଶ ହେବ । ଏହା ଫଳରେ ସହର ଗୁଡ଼ିକରେ ଘରୋଇ କାର, ବସ ଓ ସରକାରୀ କାର, ବସ୍‌ର ସଂଖ୍ୟା ବୃଦ୍ଧି ପାଉଛି । ଯାନବାହାନର ଆଧିକ୍ୟ ଯୋଗୁ ରାସ୍ତାଗୁଡ଼ିକ ଯାମ୍ ରହୁଛି । ଏହାକୁ ଦୃଷ୍ଟିରେ ରଖି ଜନ ବହୁଳ ସହରମାନଙ୍କରେ ଭାରତ ସରକାର 2006 ମସିହାରେ **ଜାତୀୟ ସହରୀ ପରିବହନ ନୀତି** (NUTP) ପ୍ରଣୟନ କରିଛନ୍ତି । ବର୍ତ୍ତମାନ କୋଲକାତା, ଦିଲ୍ଲୀ, ମୁମ୍ବାଇ, ଚେନ୍ନାଇ, ବେଙ୍ଗାଲୁରୁ, କୋଚି, ହାଇଦରାବାଦ, ଲକ୍ଷ୍ନୌ, ନାଗପୁର, ଅହମ୍ମଦାବାଦ, ଗାନ୍ଧୀନଗର, ଜୟପୁର, ଇତ୍ୟାଦି ସହରରେ ମେଟ୍ରୋଟ୍ରେନ ଚଳାଚଳ କରିବାର ସୁବିଧା ରହିଛି । ଭବିଷ୍ୟତରେ ଅନ୍ୟାନ୍ୟ ସହରମାନଙ୍କରେ ଏପ୍ରକାର ସୁବିଧା ପ୍ରଦାନ କରିବା ପାଇଁ ଯୋଜନା ଚାଲିଛି ।

ପାଇପ୍‌ଲାଇନ :-

ପାଇପ୍‌ଲାଇନ୍ ଦ୍ୱାରା ତରଳ ଓ ବାଷ୍ପୀୟ ପଦାର୍ଥ ପରିବହନ ସମ୍ଭବ । ସାଧାରଣତଃ ପାଇପ୍‌ଲାଇନ ଦ୍ୱାରା ସହର ଓ ଶିଳ୍ପ କେନ୍ଦ୍ରଗୁଡ଼ିକୁ ଜଳଯୋଗାଣ କରାଯାଏ । ମାତ୍ର ଏବେ ପାଇପଲାଇନ ଦ୍ୱାରା ଅଶୋଧିତ ଖଣିଜ ତୈଳ (Crude oil) ପେଟ୍ରୋଲିୟମ ଉତ୍ପାଦ, ଖଣିଜ ତୈଳ ଓ ପ୍ରାକୃତିକ ଗ୍ୟାସ ଉତ୍ପାଦନ କ୍ଷେତ୍ର ବିଶୋଧନାଗାର ଏବଂ ବୃହତ ତାପଜ ବିଦ୍ୟୁତ କେନ୍ଦ୍ରଗୁଡ଼ିକୁ ଯୋଗାଇ ଦିଆଯାଉଛି । ଏହା ବ୍ୟତୀତ କଠିନ ପଦାର୍ଥ କୋଇଲା, ଖଣିଜ ପଦାର୍ଥ ପ୍ରଭୃତି ମଧ୍ୟ ପରିବହନ କରାଯାଉଛି । ଏହା ଦ୍ୱାରା ଖର୍ଚ୍ଚ କମ୍ ପଡୁଛି । ରନ୍ଧନଗ୍ୟାସ ମଧ୍ୟ ପାଇପଲାଇନ୍ ଦ୍ୱାରା ଉପଭୋକ୍ତାମାନଙ୍କୁ ଯୋଗାଇ ଦିଆଯାଉଛି ।

ଭାରତରେ କେତେକ ଅଞ୍ଚଳରେ ପାଇପ ଲାଇନ ଦ୍ୱାରା ପରିବହନ ବ୍ୟବସ୍ଥା ଅଛି ।

1. ନହର କଟିଆ - ନୁନାମାଟି - ବରାଉଣୀ ପାଇପ୍ ଲାଇନ:

ଏହା ଭାରତର ସର୍ବପ୍ରଥମ ପାଇପ ଲାଇନ । ଏହା ପ୍ରଥମେ ଆସାମର ନହାର କଟିଆଠାରୁ ନୁନାମାଟି ପର୍ଯ୍ୟନ୍ତ ଯାଇଥିଲା। ପରେ ଏହା ଗୁଆହାଟୀ (ଆସାମ) ଦେଇ ବରାଉଣୀ (ବିହାର) ପର୍ଯ୍ୟନ୍ତ ଏବଂ ତା'ପରେ ଏଲ୍ଲାହାବାଦ (ଉତ୍ତରପ୍ରଦେଶ) ଦେଇ କାନପୁର ପର୍ଯ୍ୟନ୍ତ ଯାଇଛି । ଏଥିରୁ ଛଅଗୋଟି ଶାଖା ଲାଇନ ବାହାରି ବିଭିନ୍ନ ସ୍ଥାନକୁ ଯାଇଛି । ତନ୍ମଧ୍ୟରୁ ନୁନାମାଟି-ସିଲିଗୁରି, ବଉରଣୀ-ହଳିଦଆ - କାନପୁର ପାଇପ୍‌ଲାଇନ୍ ଉଲ୍ଲେଖନୀୟ ।

2. ସାଲାୟା - କୋୟାଲି - ମଥୁରା ପାଇପ ଲାଇନ: ଗୁଜୁରାଟ ଅନ୍ତର୍ଗତ କଚ୍ଛର ସାଲାୟା ଠାରୁ ମଥୁରା ପର୍ଯ୍ୟନ୍ତ ଏବଂ ପରେ ଏହା ଦିଲ୍ଲୀ ଓ ପାନିପତ୍ ଦେଇ ଜଳନ୍ଧର (ପଞ୍ଜାବ) ପର୍ଯ୍ୟନ୍ତ ବିସ୍ତୃତ । ଏହାର ଏକ ଶାଖାଲାଇନ୍ କୋୟାଲି (ଗୁଜରାଟ) ପର୍ଯ୍ୟନ୍ତ ଲମ୍ବିଛି ।

3. ହାଜରା - ଜଗଦୀଶ ପୁର ପାଇପଲାଇନ୍ :

ଗୁଜରାଟର ହାଜରାଠାରୁ ଉତ୍ତରପ୍ରଦେଶର ଜଗଦୀଶପୁର ଦେଇ ମଧ୍ୟପ୍ରଦେଶର ବିଜୟପୁର ପର୍ଯ୍ୟନ୍ତ ଏକ ପାଇପଲାଇନ ଯାଇଛି, ଏଥିରୁ ଏକ ଶାଖାଲାଇନ୍ ଉତ୍ତରପ୍ରଦେଶର ସାହାଜାହାନ୍‌ପୁର ମଧ୍ୟଦେଇ ମୁମ୍ବାଇ ପର୍ଯ୍ୟନ୍ତ ସଂପ୍ରସାରିତ ହୋଇଛି ।

4. ମୁମ୍ବାଇ ହାଇ ମୁମ୍ବାଇ - ଆଙ୍କ୍‌ଲେଶ୍ୱର - କୋୟାଲି ପାଇପ୍‌ଲାଇନ୍ :

'ମୁମ୍ବାଇହାଇ'କୁ ମୁଖ୍ୟ ଭୂଖଣ୍ଡସ୍ଥ ମୁମ୍ବାଇ ସହିତ ସଂଯୋଗ କରି ପୁଣେ ପର୍ଯ୍ୟନ୍ତ ଏହି ପାଇପଲାଇନ ଯାଇଅଛି । ଏହା ଗୁଜରାଟର ଆଙ୍କଲେଶ୍ୱର ଓ କୋୟାଲିକୁ ମଧ୍ୟ ସଂଯୋଗ କରିଅଛି ।

5. କାଣ୍ଡଲା- ଭାଟିଣ୍ଡା ପାଇପ୍ ଲାଇନ୍ : ଏହାର ଏକ ଶାଖା ମୁମ୍ବାଇରୁ ମାନ୍‌ମାଡ଼ ପର୍ଯ୍ୟନ୍ତ ଯାଇଅଛି ।

6. ବିଶାଖାପାଟଣା ଠାରୁ ବିଜୟୱାଡ଼ା ପାଇପ ଲାଇନ

7. ମାଙ୍ଗାଲୋର ଠାରୁ ବେଙ୍ଗାଲୁରୁ ଦେଇ ଚେନ୍ନାଇ ପର୍ଯ୍ୟନ୍ତ ।

8. ହଳଦିଆ ରୁ ପାରାଦୀପ ପର୍ଯ୍ୟନ୍ତ ପାଇପ ଲାଇନ୍ ସଂଯୋଗ କାର୍ଯ୍ୟ ନିର୍ମାଣାଧୀନ ଅଛି ।

କଠିନ ଖଣିଜ ପଦାର୍ଥ ପରିବହନକାରୀ ପାଇପ ଲାଇନ (Slurry Pipelines):

1. ଛତିଶଗଡ଼ର ବଇଲାଡ଼ିଲା ଓ ଆନ୍ଧ୍ରପ୍ରଦେଶର ବିଶାଖାପାଟଣା ମଧ୍ୟରେ ଲୁହାପଥର ପରିବହନ ପାଇଁ ପାଇପ ଲାଇନ

2. କର୍ଣ୍ଣାଟକର ଦରମୁଖରୁ ଲୁହାପଥର ମାଙ୍ଗାଲୋର ବନ୍ଦରକୁ ପରିବହନ କରାଯାଇଛି ।

3. ରାଜସ୍ଥାନର ଦେବାର ଉଦୟପୁର ପାଇପଲାଇନ ସାହାଯ୍ୟରେ ଜିଙ୍କ (Zinc) ଖଣିଜ ପଦାର୍ଥ ଓ ଜିଙ୍କ ଉତ୍ପାଦ ପରିବହନ କରାଯାଉଛି ।

ଜଳପଥ ପରିବହନ :

ଅନ୍ତଃସ୍ଥଳୀୟ ଜଳପଥ : ଭାରତ ପୃଥିବୀର ଏକ ବୃହତ୍ତମ ଉପଦ୍ୱୀପ । ଏହାର 7516 କି.ମି.ରୁ ଊର୍ଦ୍ଧ୍ୱ ଉପକୂଳ ରହିଛି । ଏଥିରେ 7ଟି ମୁଖ୍ୟ ବନ୍ଦର 250ଟି କ୍ଷୁଦ୍ରବନ୍ଦର ରହିଛି । ହ୍ରଦ ପଶ୍ଚାତ ଜଳ (Back Water), ନିବେଶିକା (Creek) ନଦୀ ଓ କେନାଲ ଦ୍ୱାରା ପରିବହନକୁ **ଅନ୍ତସ୍ଥଳୀୟ ପରିବହନ** କୁହାଯାଏ । ଜଳ ପରିବହନ ସବୁଠୁ ଶସ୍ତା । ବୃହଦାକାର ଏବଂ ଓଜନିଆ (ଭାରୀ) ଜିନିଷ ନେବା ଆଣିବା ପାଇଁ ଜଳ ପରିବହନ ସୁବିଧାଜନକ । ଏହା ଏକ ଜାଳେଣୀ-ସମର୍ଥ ଓ ପରିବେଶ - ଅନୁକୂଳ ପରିବହନ ମାଧ୍ୟମ ।

ଭାରତରେ ପ୍ରାୟ 14500 କି.ମି. ଦୈର୍ଘ୍ୟ ଆନ୍ତର୍ଦ୍ଦେଶୀୟ ବା ଅନ୍ତଃସ୍ଥଳୀୟ ଜଳପଥ ଅଛି । ଏଥରୁ ମାତ୍ର 3700 କି.ମି. ସୁନାବ୍ୟା । ଏହାଦ୍ୱାରା ବାର୍ଷିକ ପ୍ରାୟ 45 ନିୟୁତ ଟନ୍ ମାଲ ପରିବହନ କରାଯାଇଥାଏ ।

ଏହା ବ୍ୟତୀତ ଅନ୍ତର୍ଦ୍ଦେଶୀୟ ଜଳପଥ ଭାରତ ଓ ବଙ୍ଗଳାଦେଶ ମଧ୍ୟରେ 1972 ମସିହାଠାରୁ କାର୍ଯ୍ୟକାରୀ ହେଉଛି । ଏସବୁକୁ 1994ରେ ନବୀକରଣ କରାଯାଇଛି । ସେଗୁଡ଼ିକ ହେଲା କ) କୋଲକାତା - ପାଣ୍ଡୁ, ଖ) - କୋଲକାତା - କରିମ୍‌ଗଞ୍ଜ (ଗ) ରାଜସାହି - ଧୁଲିଆନା ଏବଂ (ଘ) ପାଣ୍ଡୁ - କରିମ ଗଞ୍ଜ ।

ଅଧୁନା ଆରବ ସାଗର ଓ ବଙ୍ଗୋପସାଗରକୁ ସଂଯୋଗ କରିବା ପାଇଁ ପକ୍ ପ୍ରଣାଳୀ ମଧ୍ୟଦେଇ ରାମସେତୁ ଯୋଜନା କରାଯାଇଛି । ଯଦ୍ୱାରା ଭାରତର ପୂର୍ବ ଉପକୂଳସ୍ଥ ବନ୍ଦରଗୁଡ଼ିକ ପଶ୍ଚିମ ଉପକୂଳ ବନ୍ଦରଗୁଡ଼ିକ ସହିତ ସଂଯୋଗ ହୋଇପାରିବ ।

ଏହାବ୍ୟତୀତ କେତେକ ମୁଖ୍ୟ କେନାଲ ଦ୍ୱାରା ମଧ୍ୟ ଅନ୍ତସ୍ଥଳୀୟ ପରିବହନ କରାଯାଇଥାଏ । ସେଗୁଡ଼ିକ ହେଲା

କ) ବକିଂହାମ କେନାଲ - କୋମାନୁର କେନାଲଠାରୁ କୃଷ୍ଣା ନଦୀ ତ୍ରିକୋଣଭୂମିରେ ଅବସ୍ଥିତ ମୀରାକାନମ୍ ପର୍ଯ୍ୟନ୍ତ

ଖ) କୁମ୍ବର ଜୁଆ କେନାଲ - ମାଣ୍ଡୋବୀ ନଦୀ ଓ ଜୁଆର ନଦୀକୁ ସଂଯୋଗ କରେ ।

ଗ) ବଦାରନିୟମ କେନାଲ ନାଗା ପଟ୍ଟିନମ ବନ୍ଦରକୁ ବଦାରନିୟମ ସହିତ ସଂଯୋଗ କରେ

ଘ) ନର୍ମଦା - ତାପ୍ତୀ ନଦୀର ମୁହାଣକୁ ସଂଯୋଗ କରେ

ଙ) ପଶ୍ଚିମରେ ଆରବ ସାଗରକୁ ପ୍ରବାହିତ ନଦୀଗୁଡ଼ିକର ନିବେଶଗୁଡ଼ିକୁ ସଂଯୋଗ କରେ ।

ସମୁଦ୍ରପଥ :

ଭାରତର ବହିର୍ବାଣିଜ୍ୟ ଓ ଉପକୂଳବର୍ତ୍ତୀ ବାଣିଜ୍ୟ କାରବାର ସମୁଦ୍ରପଥ ଦେଇ ହୋଇଥାଏ । ଭାରତର ମୂଳ ଭୂଖଣ୍ଡ ଉପକୂଳ ରେଖାର ଦୈର୍ଘ୍ୟ 6100 କି.ମି. । ଏହି ତଟରେଖାରେ ଦେଶର 12ଟି ପ୍ରଧାନ ବନ୍ଦର ଯଥା, କୋଲକାତା, ହଳଦିଆ, ପାରାଦ୍ୱୀପ, ବିଶାଖାପାଟଣା, ଏନୋର୍, ଚେନ୍ନାଇ, ନିଉ ତୁତିକୋରିନ୍, କୋଚି, ନିଉ ମାଙ୍ଗାଲୋର, ମର୍ମାଗାଓ, ମୁମ୍ବାଇ, କାଣ୍ଡଲା ଓ ନବସେବା ରହିଛି । ଏହା ବ୍ୟତୀତ 200ଟି କ୍ଷୁଦ୍ର ଓ ମଧ୍ୟମ ଧରଣର ବନ୍ଦର ମଧ୍ୟ ଅଛି । ବୃହତ୍ ବନ୍ଦରଗୁଡ଼ିକ ଦେଶର ମୋଟ ବୈଦେଶିକ ବାଣିଜ୍ୟର ଶତକଡ଼ା 95ଭାଗ ପରିଚାଳନା କରିଥାନ୍ତି । ଭାରତୀୟ ଜାହାଜନିଗମ (Shipping corporation of India) ଦେଶର ବାଣିଜ୍ୟ କାରବାର ଓ ଜାହାଜ ପରିଚାଳନା ପାଇଁ ଏକ ମାତ୍ର ରାଷ୍ଟ୍ରାୟତ୍ତ କମ୍ପାନୀ । ଅନ୍ୟାନ୍ୟ ଘରୋଇ ଜାହାଜ କମ୍ପାନୀ ମଧ୍ୟ ଜାହାଜ ପରିବହନ କ୍ଷେତ୍ରରେ କାର୍ଯ୍ୟ କରୁଛନ୍ତି ।

ଭାରତର ସାମୁଦ୍ରିକ ବର୍ହି ବାଣିଜ୍ୟ କାରବାର ମୁଖ୍ୟତଃ ଚାରିଗୋଟି ସମୁଦ୍ର ପଥ ଦେଇ ହୋଇଥାଏ ।

1. ଇଉରୋପ ମହାଦେଶର ଦେଶଗୁଡ଼ିକ ସହ ଭାରତ ସୁଏଜ କେନାଲ ପଥ ଦେଇ ବାଣିଜ୍ୟ କାରବାର କରିଥାଏ ।

2. ପଶ୍ଚିମ ଆଫ୍ରିକୀୟ ଦେଶ ଓ ଦକ୍ଷିଣ ଆମେରିକୀୟ ଦେଶ ସମୂହ ସହିତ ଉତ୍ତମାଶା ଅନ୍ତରୀପ (Cape of Good Hope) ପଥ ଦେଇ ବାଣିଜ୍ୟ କାରବାର କରାଯାଇଥାଏ ।

3. ସିଂଗାପୁର ସମୁଦ୍ର ପଥଦେଇ ଭାରତ ଦକ୍ଷିଣ-ପୂର୍ବ ଏସିଆ, ଜାପାନ, ଯୁକ୍ତରାଷ୍ଟ୍ର ଆମେରିକା ଓ କାନାଡ଼ା ସହିତ ବାଣିଜ୍ୟ କାରବାର କରିଥାଏ ।

4. ମଲ୍ଲକା ପ୍ରଣାଳୀ ପଥଦେଇ ଅଷ୍ଟ୍ରେଲିଆ ଓ ନିଉଜଲାଣ୍ଡ ସହିତ ବାଣିଜ୍ୟ କାରବାର ଚାଲେ ।

ମୁମ୍ବାଇ ବନ୍ଦର ମଧ୍ୟ ଦେଇ ସବୁଠାରୁ ଅଧିକ ଯାତ୍ରୀ ଓ ପଣ୍ୟଦ୍ରବ୍ୟ ଯାଅ ଆସ କରିଥାଏ । ତେଣୁ ମୁମ୍ବାଇକୁ **ଭାରତର ପ୍ରବେଶ ଦ୍ୱାର** (Gateway of India) କହିବାର ଯଥାର୍ଥତା ଅଛି । ଆମଦେଶର ବନ୍ଦର ଗୁଡ଼ିକ ମଧ୍ୟ ଦେଇ ରପ୍ତାନି ଠାରୁ ଆମଦାନି ଅଧିକ ହୋଇଥାଏ । କେବଳ କଞ୍ଚାମାଲ ରପ୍ତାନି ନ କରି ଦେଶରେ ଉତ୍ପାଦିତ ଦ୍ରବ୍ୟ ରପ୍ତାନି କଲେ ଆମର ଜାତୀୟ ଆୟ ବୃଦ୍ଧି ପାଇବ ଓ ଲୋକମାନଙ୍କର ଜୀବନ ଧାରଣମାନ ଉନ୍ନତ ହୋଇପାରିବ ।

ଆକାଶ ପଥ :

ଆକାଶ ପଥରେ ଯାତ୍ରା ସବୁଠାରୁ କମ୍ ସମୟ ଲାଗେ ମାତ୍ର ଏହା ବ୍ୟୟ ବହୁଳ । ଅଗମ୍ୟ, ଦୂରଦୂରାନ୍ତର ଏବଂ ବିପଦଶଙ୍କୁଳ ସ୍ଥାନମାନଙ୍କୁ ଆକାଶ ପଥରେ ପହଞ୍ଚିବା ସୁବିଧା ଜନକ । ସେଥିପାଇଁ ପ୍ରାକୃତିକ ବିପର୍ଯ୍ୟୟ, ବନ୍ୟା, ଦୁର୍ଭିକ୍ଷ, ଭୂମିକମ୍ପ, ମହାମାରୀ ଓ ଯୁଦ୍ଧ ସମୟରେ ଆକାଶ ପଥ ପରିବହନ ନିର୍ଣ୍ଣାୟକ ଭୂମିକା ଗ୍ରହଣ କରିଥାଏ । ସ୍ୱାଧୀନତା ପୂର୍ବରୁ ଆକାଶ ପରିବହନ ଘରୋଇ କମ୍ପାନୀମାନଙ୍କ ଦ୍ୱାରା ପରିଚାଳିତ ହେଉଥିଲା । 1953 ମସିହାରେ ବେସାମରିକ ବାୟୁ ପରିବହନ ଜାତୀୟକରଣ କରାଯାଇ **ଏୟାର ଇଣ୍ଡିଆ** (AI) ଏବଂ **ଇଣ୍ଡିଆନ୍ ଏୟାରଲାଇନସ୍** (IA) ନାମରେ ଦୁଇଟି ନିଗମ ସ୍ଥାପିତ ହେଲା । ବର୍ତ୍ତମାନ ଏହି ଦୁଇଟି ସଂସ୍ଥା ମିଳିତଭାବେ **ଏୟାର ଇଣ୍ଡିଆ** ନାମରେ କାର୍ଯ୍ୟ ସଂପାଦନ କରୁଛି ।

ସାଧାରଣ ଯାତ୍ରୀ ଓ ମାଲ ସରବରାହ କାମ ବେସାମରିକ ବିମାନ ଚଳାଚଳ ନିଗମ ଦାୟିତ୍ୱରେ ଆନ୍ତର୍ଜାତିକ ବେସାମରିକ ବିମାନ ସେବା **ଏୟାର ଇଣ୍ଡିଆ** ଦ୍ୱାରା ନିର୍ବାହ ହୋଇଥାଏ । ମାତ୍ର ଦ୍ୱିତୀୟ ନିଗମଟି ଦେଶର ଆଭ୍ୟନ୍ତରୀଣ ବିମାନ ଚଳାଚଳ ଦାୟିତ୍ୱ ସହ ମଧ୍ୟପ୍ରାଚ୍ୟ ଓ ଦକ୍ଷିଣ ପୂର୍ବ ଏସିଆର ଦେଶଗୁଡ଼ିକ ସହ ବିମାନ ପରିଚାଳନା କରିଥାଏ । ଅଧୁନା ଭାରତରେ 123 ଟି ବିମାନ ବନ୍ଦର ରହିଛି ।

ଭାରତ
ପ୍ରମୁଖ ବନ୍ଦର ଓ ବିମାନ ବନ୍ଦର
N
ଶ୍ରୀନଗର
ଅମୃତସର
ପାକିସ୍ତାନ
ଚୀନ୍
ନେପାଳ
ଦିଲ୍ଲୀ
ଜୟପୁର
ଭୁଟାନ
ଗୌହାଟି
ମିଆଁମାର
ବାଂଲା ଦେଶ
କାଣ୍ଡଲା
ଅହମଦାବାଦ
କୋଲକାତା
ହଳଦିଆ
କୋଲକାତା ବନ୍ଦର
ପାରାଦ୍ୱୀପ
ଭୁବନେଶ୍ୱର
ମୁମ୍ବାଇ ବନ୍ଦର
ମୁମ୍ବାଇ
ନବସିବା
ହାଇଦ୍ରାବାଦ
ବିଶାଖାପାଟଣା
ବଙ୍ଗୋପସାଗର
ପାଣାଜୀ
ମାର୍ମାଗାଓ
ଆରବ ସାଗର
ବେଙ୍ଗାଲୁରୁ
ଏନ୍ନୋର
ଚେନ୍ନାଇ
ନିଉ ମାଙ୍ଗାଲୋର
ଚେନ୍ନାଇ ବନ୍ଦର
କୋଚି
ନୂଆ ତୁତିକୋରିନ
ଲାକ୍ଷାଦ୍ୱୀପ
କୋଚି ବନ୍ଦର
ଥିରୁଅନନ୍ତପୁରମ
ଶ୍ରୀଲଙ୍କା
ଆଣ୍ଡାମାନ ଓ ନିକୋବର
ଭାରତ ମହାସାଗର
ସୂଚନା
ବିମାନ ବନ୍ଦର
ବନ୍ଦର
East of Greenwich
PROJECTION -UTM
DATUM - WGS_1984

ଚିତ୍ର : 22

ଏଥିରେ ୩୪ ଟି ଆନ୍ତର୍ଜାତୀୟ ବିମାନବନ୍ଦର ରହିଛି ।
(ଚିତ୍ର : 22 ଦେଖ)

ବର୍ତ୍ତମାନ ଭାରତର ଆକାଶ ପଥରେ ଘରୋଇକମ୍ପାନୀମାନଙ୍କ ପାଇଁ ଖୋଲା ଯାଇଥିବାରୁ ଅନେକ କମ୍ପାନୀ ବ୍ୟବସାୟ ଆରମ୍ଭ କରିଛନ୍ତି । ସେଗୁଡ଼ିକ ମଧ୍ୟରେ **ସାହାରା ଏୟାରଲାଇନ୍‌ସ, ଡେକାନ୍ ଚାଟର, ବିସ୍ତାରା, ଏୟାର ଏସିଆ, ଜେଟ୍ ଏୟାରଲାଇନ୍‌ସ, ଇଣ୍ଡିଗୋ (Indigo) ଗୋ ଏୟାର (Go Air)** ଆଦି ମୁଖ୍ୟ ।

ବେସାମରିକ ବିମାନ ସେବା କ୍ଷେତ୍ରରେ ଦୁଇ ପ୍ରକାର ବିମାନ ବନ୍ଦର କାର୍ଯ୍ୟକରୁଛି । ଯଥା :- **ଆନ୍ତର୍ଜାତୀୟ ବିମାନବନ୍ଦର ଓ ଘରୋଇ ବିମାନ ବନ୍ଦର** । ଆନ୍ତର୍ଜାତୀୟ ବିମାନବନ୍ଦରଗୁଡ଼ିକ ଦିଲ୍ଲୀ, ମୁମ୍ବାଇ, ଚେନ୍ନାଇ, କୋଲକାତା, ବେଙ୍ଗାଲୁରୁ, ହାଇଦ୍ରାବାଦ, ଅହମଦାବାଦ, ଜୟପୁର, ଅମୃତସର, ଗୁଆହାଟି, ଥିରୁଅନନ୍ତପୁରମ୍, ପାଣାଜୀ, କୋଚି, ଶ୍ରୀନଗର ଇତ୍ୟାଦିରେ ଅବସ୍ଥିତ । ଦେଶରେ 63 ଟି ଆଭ୍ୟନ୍ତରୀଣ ବା ଘରୋଇ ବିମାନ ବନ୍ଦର ଅଛି । ଏଗୁଡ଼ିକର ପରିଚାଳନା ଦାୟିତ୍ୱ **ଭାରତୀୟ ବିମାନ ବନ୍ଦର ପ୍ରାଧିକରଣ** (Airport Authority of India) ସଂସ୍ଥା ଉପରେ ନ୍ୟସ୍ତ ।

ବର୍ତ୍ତମାନ ଦେଶର ବିମାନ ବନ୍ଦରଗୁଡ଼ିକୁ ଘରୋଇ କରଣ କରାଯାଇ ଯାତ୍ରୀମାନଙ୍କୁ ଅଧିକ ସୁବିଧା ଓ ନିରାପତ୍ତା ପ୍ରଦାନ କରିବାର ବ୍ୟବସ୍ଥା କରାଯାଉଛି । ରାତ୍ରୀକାଳରେ ମଧ୍ୟ ବିମାନ ଅବତରଣ ଓ ଉଡ଼ାଣ ବ୍ୟବସ୍ଥା କାର୍ଯ୍ୟକାରୀ କରାଯାଉଛି ।

ଯୋଗାଯୋଗ :- ଯୋଗାଯୋଗ ମନୁଷ୍ୟର ଜୀବନ ଧାରଣ ପାଇଁ ଅତ୍ୟନ୍ତ ଜରୁରୀ, ପରସ୍ପର ସମ୍ପର୍କ ବିନା ମନୁଷ୍ୟ ବଞ୍ଚିରହିବା କଷ୍ଟକର । ପୂର୍ବକାଳରେ ମନୁଷ୍ୟ ମନୁଷ୍ୟ ମଧ୍ୟରେ ସମ୍ପର୍କ କମ୍ ଥିଲା ଏବଂ ଏହା ସାଙ୍କେତିକ ଭାଷା ବା ପ୍ରତ୍ୟକ୍ଷ କଥାବାର୍ତ୍ତାରେ ହିଁ ସମ୍ଭବ ହେଉଥିଲା । ବର୍ତ୍ତମାନ ଯୋଗାଯୋଗ ବୃଦ୍ଧି ପାଇଛି ଏବଂ ମାଧ୍ୟମ ମଧ୍ୟ ପରିବର୍ତ୍ତିତ ହୋଇଛି । ମନୁଷ୍ୟର ଗତିଶୀଳତା ଓ ଜିନିଷ ପତ୍ରର ପରିବହନ, ଯୋଗାଯୋଗ ମାଧ୍ୟମରେ ବୃଦ୍ଧି ଏବଂ ପରିବର୍ତ୍ତନ ଆଣିଛି । ବର୍ତ୍ତମାନ ଆମେ ଟେଲିଫୋନ୍, ଫ୍ୟାକ୍ସ, ଟେଲିଭିଜନ, ମୋବାଇଲ ଫୋନ, ଓ୍ୟାରଲେସ ଏବଂ ଇଣ୍ଟରନେଟ୍ ମାଧ୍ୟମରେ ମୁହୂର୍ତ୍ତକ ମଧ୍ୟରେ ପୃଥିବୀର ଯେକୌଣସି ସ୍ଥାନରେ ଘଟୁଥିବା ଘଟଣାବଳୀର ସୂଚନା ପାଇ ପାରୁଛୁ । ପରିବହନ ଓ ଯୋଗାଯୋଗର ଉନ୍ନତି ଯୋଗୁଁ ଆଜି ଦୂରତ୍ୱ ହ୍ରାସ ପାଇଛି ଏବଂ ପୃଥିବୀ ସଂକୁଚିତ ହେବାରେ ଲାଗିଛି । ଯୋଗାଯୋଗକୁ ଦୁଇଟି ଭାଗରେ ବିଭକ୍ତ କରାଯାଇପାରେ ଗୋଟିଏ ହେଲା **ବ୍ୟକ୍ତିଗତ** (Personal Communication) **ଯୋଗାଯୋଗ** ଓ ଅନ୍ୟଟି ହେଲା **ଗଣଯୋଗାଯୋଗ** (Mass Communication) ।

ବ୍ୟକ୍ତିଗତ ଯୋଗାଯୋଗ (Personal Communication) : ଆମ ଦେଶରେ ଡାକ ସେବା କାର୍ଯ୍ୟ 1854 ମସିହାରେ ଦେଶର ବିଭିନ୍ନ ଅଞ୍ଚଳରେ କାର୍ଯ୍ୟ କରୁଥିବା 700 ଡାକ ଘରକୁ ନେଇ ଭାରତ ସରକାରଙ୍କ 'ଡାକବିଭାଗ'ତତ୍ତ୍ୱାବଧାନରେ ଆରମ୍ଭ ହୋଇଥିଲା । ପରେ ପରେ 'ତାରସେବା କାର୍ଯ୍ୟକୁ ସାମିଲକରି 'ଡାକ ଓ ତାର ବିଭାଗ' ମାଧ୍ୟମରେ ଉଭୟ ଡାକସେବା ଓ ତାରସେବା (Postal Netwark) ସମ୍ପାଦିତ ହେଲା । 1984 ମସିହାରେ ଡାକ ଓ ତାର ବିଭାଗକୁ 'ଡାକବିଭାଗ' ଓ ଦୂରସଞ୍ଚାର' (Tele Communication) ବିଭାଗ ନାମକ ଦୁଇଟି ବିଭାଗରେ ବିଭକ୍ତ କରାଯାଇଥିଲା ।

ଡାକ ବିଭାଗ ଜନସାଧାରଣଙ୍କୁ ବିଭିନ୍ନ ସେବା ଯୋଗାଇଥାଏ । ଚିଠିପତ୍ର, ପାର୍ସଲ, ବିତରଣ ଏହାର ପ୍ରଧାନକାମ । ଦେଶ ଭିତରେ ଚିଠିପତ୍ର ବିତରଣ ଦାୟିତ୍ୱ ନିର୍ବାହ କରିବା ସହ ଡାକ ବିଭାଗ ବିଦେଶକୁ ଚିଠି ପତ୍ର ପଠାଇବା ଓ ବିଦେଶରୁ ଆସୁଥିବା ଚିଠିପତ୍ରକୁ ଯଥାସ୍ଥାନରେ ପହଞ୍ଚାଇବା କାମ କରିଥାଏ । ସ୍ୱାଧୀନତା ପରେ ଟେଲିଫୋନ ସେବା ମଧ୍ୟ ଉଲ୍ଲେଖନୀୟ ଭାବେ ବୃଦ୍ଧି ପାଇଛି । ସମସ୍ତ ମହାନଗରୀ, ସମସ୍ତ ସହର ଏବଂ ବଡ଼ ବଡ଼ ଗ୍ରାମରେ ଏବେ ଟେଲିଫୋନ୍ ସେବା ଉପଲବ୍ଧ ହେଉଅଛି । ଦେଶ ଭିତରେ ଟେଲିଫୋନ୍ ସେବାର ପ୍ରସାର ଘଟିବା ସଙ୍ଗେ ପୃଥିବୀର ଅନେକ ଦେଶ ସହିତ ଟେଲିଫୋନ୍ ସମ୍ପର୍କ ସ୍ଥାପିତ ହୋଇଛି । ଏବେ ଦେଶରେ ବଡ଼ ବଡ଼ ସହରରେ ରହୁଥିବା ଲୋକେ ଅନେକ ବିଦେଶୀ ରାଷ୍ଟ୍ରସହ ସିଧାସଳଖ ISD (International Subscriber Dialling) ମାଧ୍ୟମରେ ଟେଲିଫୋନ ସମ୍ପର୍କ ସ୍ଥାପନ କରି ପାରୁଛନ୍ତି । ଏତଦ୍ ବ୍ୟତୀତ ଟେଲିକମ୍ (ମୋବାଇଲ, Internet ଇତ୍ୟାଦି) ସେବା ବ୍ୟବସ୍ଥା ପ୍ରଚଳନ କରାଯାଇଅଛି ।

ଗଣଯୋଗାଯୋଗ (Mass Communicetion) :

ଜନସାଧାରଣଙ୍କୁ ଦେଶର ବିଭିନ୍ନ ନୀତି ଓ ଯୋଜନା ସମ୍ବନ୍ଧରେ ଅବଗତ କରାଇବା ଦିଗରେ ଗଣ ମାଧ୍ୟମ ଏକ ଗୁରୁତ୍ୱ ପୂର୍ଣ୍ଣ ଭୂମିକା ନିର୍ବାହ କରିଥାଏ । ସମ୍ବାଦ ପରିବେଷଣ ସହ ବିଭିନ୍ନ ପ୍ରକାର ମନୋରଞ୍ଜନ କାର୍ଯ୍ୟକ୍ରମ ମଧ୍ୟ ପରିବେଷଣ କରିଥାଏ । ରେଡ଼ିଓ, ଟି.ଭି., ସମ୍ବାଦପତ୍ର, ମାଗାଜିନ୍, ବହି ଏବଂ ଫିଲ୍ମ ଗଣଯୋଗାଯୋଗର ପ୍ରଧାନ ମାଧ୍ୟମ । ଏହାଦ୍ୱାରା ଅନେକ ଲୋକଙ୍କୁ ଏକ ସମୟରେ ସେବା ଯୋଗାଇ ଦିଆଯାଇପାରୁଛି । ତେଣୁ ଏହାକୁ **ଗଣମାଧ୍ୟମ** କୁହାଯାଏ ।

ପ୍ରସାର ଭାରତୀ (Broadcasting Corporation of India) ଭାରତ ସରକାରଙ୍କ ଦ୍ୱାରା ପରିଚାଳିତ ଏବଂ ଗଣମାଧ୍ୟମ ସଂସ୍ଥା ଆକାଶବାଣୀ (All India Radio) ଏବଂ ଦୂର ଦର୍ଶନ ଏହାର ଦୁଇଟି ବିଭାଗ ।

* **ଦେଶରେ ଆକାଶବାଣୀ** (All India Radio) ପ୍ରାୟ 200ଟି ଷ୍ଟେସନ୍ କାମ କରୁଛି । ଜାତୀୟ ଓ ପ୍ରାନ୍ତୀୟ ଭାଷାରେ ବିଭିନ୍ନ କାର୍ଯ୍ୟକ୍ରମ, ସହର ଓ ଗ୍ରାମାଞ୍ଚଳ ପାଇଁ ପରିବେଷଣ କରିଥାଏ । ସୈନ୍ୟବାଭାଗ, ମହିଳା ଓ ଶିଶୁ, ଯୁବଗୋଷ୍ଠୀ, ଛାତ୍ରସମାଜ, ଆଦିବାସୀ ସଂପ୍ରଦାୟ ତଥା ଶିଳ୍ପ ଶ୍ରମିକମାନଙ୍କ ପାଇଁ ବିଶେଷ କାର୍ଯ୍ୟକ୍ରମ ମଧ୍ୟ ପ୍ରଚାର କରାଯାଉଇ ।

* **ଦୂରଦର୍ଶନ** (Television) ପୃଥିବୀର ଏକ ବୃହତ୍ ଗଣମାଧ୍ୟମ ସଂସ୍ଥା । ଏହା ଦୃଶ୍ୟମାନ ମାଧ୍ୟମ ହୋଇଥିବାରୁ ଲୋକମାନଙ୍କ ମନରେ ପ୍ରଭୂତ ପ୍ରଭାବ ପକାଇ ସର୍ବଶ୍ରେଷ୍ଠ ଶକ୍ତିଶାଳୀ ମାଧ୍ୟମର ମାନ୍ୟତା ଲାଭ କରିଛି । ଆମ ଦେଶର ଶତକଡ଼ା ପ୍ରାୟ 90 ଭାଗ ଜନସାଧାରଣଙ୍କ ନିକଟରେ ଦୂରଦର୍ଶନ ସେବା ଉପଲବ୍ଧ ହେଉଅଛି ।

* ପ୍ରତିବର୍ଷ ଭାରତରେ ପ୍ରାୟ 42000 ସମ୍ବାଦପତ୍ର, ପତ୍ରପତ୍ରିକା ଆଦି ପ୍ରକାଶ ପାଏ । ଏଗୁଡ଼ିକ ଦୈନିକ, ସାପ୍ତାହିକ, ମାସିକ, ତ୍ରୈମାସିକ କିମ୍ବା ବାର୍ଷିକ ସଂଖ୍ୟା ଆକାରରେ ପ୍ରକାଶ କରାଯାଇଥାଏ । ମୁମ୍ବାଇ ରୁ ପ୍ରକାଶିତ ଗୁଜରାଟି ଦୈନିକ "ମୁମ୍ବାଇ ସମାଚାର" ଦେଶର ସର୍ବପ୍ରଥମ ସମ୍ବାଦ ପତ୍ର । ଆମ ଦେଶରେ ପ୍ରାୟ 100ଟି ଭାଷାରେ ଓ ଉପଭାଷାରେ ସମ୍ବାଦପତ୍ର ପ୍ରକାଶ ପାଇଥାଏ । ହିନ୍ଦୀ ଭାଷାରେ ସବୁଠାରୁ ଅଧିକ ସଂଖ୍ୟାରେ ସଂବାଦପତ୍ର ପ୍ରକାଶ ପାଉଛି । ଏହା ପଛକୁ ଇଂରାଜୀ ଏବଂ ଉର୍ଦ୍ଦୁଭାଷାର ସ୍ଥାନ ।

* ଭାରତରେ ଚାରୋଟି **ସମ୍ବାଦ ସରବରାହ ସଂସ୍ଥା** କାର୍ଯ୍ୟ କରୁଛି । ସେଗୁଡ଼ିକ ହେଲା **ପ୍ରେସ୍‌ଟ୍ରଷ୍ଟ ଅଫ୍ ଇଣ୍ଡିଆ** (Press Trust of India), **ୟୁନାଇଟେଡ୍ ନିଉଜ୍ ଅଫ୍ ଇଣ୍ଡିଆ** (United News of India), **ସମାଚାର ଭାରତୀ** ଏବଂ **ହିନ୍ଦୁସ୍ଥାନ ସମାଚାର** । ପ୍ରଥମ ଦୁଇଟି ସରବରାହ ସଂସ୍ଥା ଇଂରାଜୀ ଭାଷାରେ ଓ ଶେଷ ଦୁଇଟି ହିନ୍ଦୀ ଭାଷାରେ ଓ ଅନ୍ୟାନ୍ୟ ଭାରତୀୟ ଭାଷାରେ ସମ୍ବାଦ ସରବରାହ କରିଥାନ୍ତି ।

* **ଚଳଚିତ୍ର (Films)** ନିର୍ମାଣରେ ଭାରତର ସ୍ଥାନ ପୃଥିବୀରେ ପ୍ରଥମ ଏହାଛଡ଼ା ଅନେକ ଭିଡ଼ିଓ ଫିଚର ଫିଲ୍ମ (Video Feature films), ଲଘୁ ଚଳଚିତ୍ର (Short films), ବୃତ୍ତଚିତ୍ର (Video Shortfilms), ଭାରତୀୟ ଭାଷାରେ ଓ ବିଦେଶରେ ନିର୍ମିତ ଚଳଚିତ୍ରକୁ ଦେଶରେ ପ୍ରଦର୍ଶନ ପାଇଁ କେନ୍ଦ୍ରୀୟ ଚଳଚିତ୍ର ପ୍ରମାଣପତ୍ର ପରିଷଦ (Central Board of Film Certification- C.B.F.C) ସଂସ୍ଥା ଅନୁମତି ପ୍ରଦାନ କରିଥାନ୍ତି ।

ଆଜିକାଲି ଟୁଇଟର, ଫେସବୁକ୍, ଇୟୁଟ୍ୟୁବ, ଇନଷ୍ଟାଗ୍ରାମ୍, ହ୍ୱାଟସ୍‌ଆପ୍ ପ୍ରଭୃତି ସାମାଜିକ ମାଧ୍ୟମ (Social media)ରେ ଅନେକ ପ୍ରକାର ବାର୍ତ୍ତା ଶୀଘ୍ର ଓ ସହଜରେ ପ୍ରସାରଣ କରାଯାଇପାରୁଛି ।

ବାଣିଜ୍ୟ (Trade) :

ଆମେ ବ୍ୟବହାର କରୁଥିବା ସମସ୍ତ ଦ୍ରବ୍ୟ ଆମେ ନିଜେ ଉତ୍ପାଦନ କରି ନ ଥାଉଁ । ଏହା ମଧ୍ୟ ସମ୍ଭବ ନୁହେଁ । ତେଣୁ ଅନ୍ୟଠାରୁ କିଣାଯାଇ ନିଜର ଚାହିଦା ପୂରଣ କରିବାକୁ ପଡ଼େ । ଆମେ ଯାହା ଠାରୁ କିଣୁ ସେ ହୁଏତ ଦ୍ରବ୍ୟ ଉତ୍ପାଦନ କରି ନଥାଇପାରେ । ଏଭଳି କିଣା ବିକା କରୁଥିବା ବ୍ୟକ୍ତିକୁ ବେପାରୀ ବା ବ୍ୟବସାୟୀ କୁହାଯାଏ । ବ୍ୟବସାୟୀମାନଙ୍କର କିଣାବିକା କାର୍ଯ୍ୟକୁ ବାଣିଜ୍ୟ ବା ବେପାର କୁହାଯାଏ । ତେଣୁ ବେପାର ଏକ ମଧ୍ୟସ୍ଥ କାର୍ଯ୍ୟ ।

ଛୋଟ ସହର, ଗ୍ରାମ ଓ ବଡ଼ ସହରମାନଙ୍କରେ ସ୍ଥାନୀୟ ବେପାର ହୁଏ । ରାଜ୍ୟ ସ୍ତରରେ ରାଜ୍ୟ ରାଜ୍ୟ ମଧ୍ୟରେ ମଧ୍ୟ ବାଣିଜ୍ୟ କରିବାର ହୁଏ । କୌଣସି ଦେଶର ବିଭିନ୍ନ ଅଞ୍ଚଳ ମଧ୍ୟରେ ହେଉଥିବା ବାଣିଜ୍ୟକୁ **ଅନ୍ତଃବାଣିଜ୍ୟ** କୁହାଯାଏ । ଦେଶ ଦେଶ ମଧ୍ୟରେ ବାଣିଜ୍ୟ ବ୍ୟବସାୟକୁ **ଅନ୍ତର୍ଦେଶୀୟ ବାଣିଜ୍ୟ** ବା **ବର୍ହିବାଣିଜ୍ୟ** କୁହାଯାଏ । ଅନ୍ତବାଣିଜ୍ୟ ଦେଶରେ

ପ୍ରଚଳିତ ମୁଦ୍ରା ମାଧ୍ୟମରେ ହେଲାବେଳେ ବର୍ହିବାଣିଜ୍ୟ ଗୋଟିଏ ଦେଶର ମୁଦ୍ରା ସହ ଅନ୍ୟ ଦେଶର ପ୍ରଚଳିତ ମୁଦ୍ରାର ବିନିମୟ ମୂଲ୍ୟରେ ଚୁକ୍ତି ହୁଏ । ବର୍ହିବାଣିଜ୍ୟ, ସ୍ଥଳ, ଜଳ ଓ ଆକାଶ ପଥ ଦେଇ ହୋଇଥାଏ । ଆନ୍ତର୍ଜାତୀୟ ବାଣିଜ୍ୟ ଦ୍ୱାରା ଦେଶର ଅର୍ଥନୀତିର ବିକାଶ ଘଟେ ।

ରପ୍ତାନି ଓ ଆମଦାନି ଆନ୍ତର୍ଜାତୀୟ ବାଣିଜ୍ୟର ପ୍ରଧାନ ଉପାଦାନ । ରପ୍ତାନି ଓ ଆମଦାନି ମଧ୍ୟରେ ଥିବା ବ୍ୟବଧାନକୁ **ବାଣିଜ୍ୟିକ ଉଦ୍‌ବୃତ୍ତି** (Balance of Trade) କୁହାଯାଏ । ଯଦି ରପ୍ତାନି କରାଯାଉଥିବା ଦ୍ରବ୍ୟର ମୂଲ୍ୟ ଆମଦାନି ହେଉଥିବା ଦ୍ରବ୍ୟର ମୂଲ୍ୟ ଠାରୁ ଅଧିକ ହୁଏ । ତେବେ ଏହା ରପ୍ତାନିକାରୀ ଦେଶ ପକ୍ଷେ ଅନୁକୂଳ ହୁଏ । ମାତ୍ର ବାଣିଜ୍ୟିକ ଉଦ୍‌ବୃତ୍ତି ଆମଦେଶ ପାଇଁ ପ୍ରତିକୂଳ ହୋଇପଡ଼ିଛି । ଅର୍ଥାତ୍ ଆମେ ରପ୍ତାନୀ କରୁଥିବା ପଣ୍ୟ ଦ୍ରବ୍ୟର ମୂଲ୍ୟ ଆମ ଦେଶକୁ ଆମଦାନି ହେଉଥିବା ଦ୍ରବ୍ୟର ମୂଲ୍ୟ ଠାରୁ କମ୍ । ଏଭଳି ପ୍ରତିକୂଳ ବ୍ୟବସ୍ଥା ବିଗତ ଶତାବ୍ଦୀର ଶେଷ ଦଶକରୁ ଲାଗିରହିଛି ।

ସ୍ୱାଧୀନତା ପୂର୍ବରୁ ଇଂଲଣ୍ଡ ଓ ରାଜ୍ୟ ଗୋଷ୍ଠୀ (Commonwealth Nations) ଦେଶଗୁଡ଼ିକ ସମେତ ଅଳ୍ପ କେତୋଟି ଅନ୍ୟ ଦେଶ ସହ ଭାରତର ବାଣିଜ୍ୟିକ ସଂପର୍କ ଥିଲା । ମାତ୍ର ଆଜି ଭାରତ ପୃଥିବୀର ପ୍ରାୟ ସମସ୍ତ ଦେଶ ଏବଂ ବାଣିଜ୍ୟିକ ଗୋଷ୍ଠୀ ସହିତ ବାଣିଜ୍ୟିକ ସଂପର୍କ ସ୍ଥାପନ କରିଛି । ପ୍ରେଟ୍ରୋଲିୟମ ଉତ୍ପାଦନକାରୀ ଦେଶ ସମୂହ, ଇଉରୋପୀୟ ଆର୍ଥନୀତିକ ଗୋଷ୍ଠୀ (EEC), ପୂର୍ବ ଇଉରୋପୀୟ ରାଷ୍ଟ୍ର, ଯୁକ୍ତରାଷ୍ଟ୍ର ଆମେରିକା, ଜାପାନ, ଋଷିଆ ଆଦି ଦେଶ ସହ ଆମର ବାଣିଜ୍ୟ କାରବାର ବିଶେଷ ଭାବେ ଚାଲିଛି ।

ଭାରତ ମୁଖ୍ୟତଃ ଶିଳ୍ପ ଜାତ ଦ୍ରବ୍ୟ, କୃଷିଭିତ୍ତିକ ପଣ୍ୟଦ୍ରବ୍ୟ, କୁଟୀର ଶିଳ୍ପଜାତ ଖଣିଜ ପିଣ୍ଡ (Ore), ଇଞ୍ଜିନିୟରିଂ ଦ୍ରବ୍ୟ, ଶସ୍ୟ ଓ ମସଲା, ଚମଡ଼ା ଜାତ ଦ୍ରବ୍ୟ, ଝୋଟଜାତ ଦ୍ରବ୍ୟ, ଧୂଆଁପତ୍ର ଓ କାଜୁ ବାଦାମ ଆଦି ବିଦେଶକୁ ରପ୍ତାନୀ କରୁଛି । ସେହିପରି ଭାରତକୁ ଆମଦାନୀ ହେଉଥିବା ପଣ୍ୟ ଦ୍ରବ୍ୟ ଗୁଡ଼ିକ ମଧ୍ୟରେ ପେଟ୍ରୋଲିୟମ୍, ପେଟ୍ରୋଲିୟମଜାତ ଦ୍ରବ୍ୟ, ମୁକ୍ତା ଏବଂ ମୂଲ୍ୟବାନ ଖଣିଜ ପଦାର୍ଥ (Precious Stones) ସୁନା, ରୂପା, ରସାୟନ ପଦାର୍ଥ ଆଦି ପ୍ରଧାନ ।

ତୁମ ପାଇଁ କାମ

ଭାରତର ପୂର୍ବ ଉପକୂଳ ଓ ପଶ୍ଚିମ ଉପକୂଳରେ ଅବସ୍ଥିତ ପ୍ରଧାନ ବନ୍ଦରଗୁଡ଼ିକର ତାଲିକା ପ୍ରସ୍ତୁତ କର ।

ସହରାଞ୍ଚଳ ଯାତ୍ରା ସମସ୍ୟା ଓ ପ୍ରତିକାର :

ବଡ଼ବଡ଼ ସହରମାନଙ୍କରେ ରାସ୍ତାଜାମ୍ ଏକ ପ୍ରମୁଖ ସମସ୍ୟା ରୂପେ ଉଭା ହୋଇଛି । ଚାରିଚକିଆ ଯାନଗୁଡ଼ିକର ଅଧିକରୁ ଅଧିକ ବ୍ୟବହାର ହିଁ ଏଥିପାଇଁ ଦାୟୀ । ଅନେକ ପ୍ରଚେଷ୍ଟା ସତ୍ତ୍ୱେ ଏହି ସମସ୍ୟାର ସମାଧାନ ବାଟ ବାହାରି ପାରୁନାହିଁ । ତେବେ, ସରକାରୀ ସ୍ତରରେ ସହର ଭିତରେ ଯାତାୟତକୁ ସହଜ କରିବା ପାଇଁ ବିଭିନ୍ନ ଯୋଜନା କରାଯାଉଛି ।

ବସ ଦ୍ରୁତ ଚାଳନା ମାର୍ଗ : ବର୍ଦ୍ଧିତ ଯାନବାହାନ ସଂଖ୍ୟା ଏବଂ ଲୋକଙ୍କର ଯାତାୟତକୁ ସହଜ କରିବା ପାଇଁ ଦେଶର ବଡ଼ ବଡ଼ ସହରମାନଙ୍କରେ ନୂତନ ଦ୍ରୁତ ପରିବହନ ମାର୍ଗ ମାନ ପରିକଳ୍ପନା କରାଯାଇଛି । ସହର ଭିତରେ ଯାତାୟତ ସହଜ ଓ ଶୀଘ୍ର ହେବା ପାଇଁ ଏହା ଉଦ୍ଦିଷ୍ଟ । ଫଳରେ ସାଧାରଣ ପରିବହନ ବ୍ୟବସ୍ଥା ପ୍ରତି ଲୋକଙ୍କ ଆଗ୍ରହ ପ୍ରକାଶ ପାଇବ ।

ଏହି ପ୍ରକଳ୍ପ କାର୍ଯ୍ୟକାରୀ ହେଲେ ସାଧାରଣ ପରିବହନ ବ୍ୟବସ୍ଥାର ବହୁଳ ବ୍ୟବହାର ସମ୍ଭବ ହୋଇପାରିବ । ତେବେ ନିମ୍ନୋକ୍ତ କେତୋଟି ଦିଗପ୍ରତି ବିଶେଷ ଧ୍ୟାନ ଦେବା ଆବଶ୍ୟକ:

(କ) ବିଭିନ୍ନ ପ୍ରୋତ୍ସାହନକାରୀ ଯୋଜନା ମାଧ୍ୟମରେ ଲୋକଙ୍କୁ ସାଧାରଣ ପରିବହନ ବ୍ୟବସ୍ଥା ବ୍ୟବହାର ପାଇଁ ଉତ୍ସାହିତ କରିବା ।

(ଖ) ଅପେକ୍ଷାକୃତ ଛୋଟ ଓ ମଧ୍ୟମ ଆକୃତି ବିଶିଷ୍ଟ କାର ବ୍ୟତୀତ ସମସ୍ତ ବଡ଼ ବଡ଼ ଯାନ (ମୋ' ବସ୍)କୁ ବସ୍ ପରିଚାଳନା ପାଇଁ ଉର୍ଦ୍ଧିଷ୍ଟ ମାର୍ଗ ବ୍ୟବହାର କରିବା ପାଇଁ ନିର୍ଦ୍ଧିଷ୍ଟ ନିୟମାବଳୀ ପ୍ରସ୍ତୁତ କରିବା ସହ ବାଧ୍ୟତା ମୂଳକ କରିବା ଆବଶ୍ୟକ । କାରଣ ବସ୍ ମାର୍ଗଟି ଦିନର ଅଧିକାଂଶ ସମୟରେ ଫାଙ୍କା ରହିଥାଏ ।

(ଗ) ଦୁଇଚକିଆ ଓ ତିନିଚକିଆ ଯାନ ଗୁଡ଼ିକ ସେମାନଙ୍କ ପାଇଁ ଉଦ୍ଦିଷ୍ଟ ମାର୍ଗରେ ଚାଲିବା ପାଇଁ କଠୋର ନିୟମ ପାଳନ ଆବଶ୍ୟକ ।

(ଘ) ଭିଡ଼ ରାସ୍ତା ପାରିହେବା ପାଇଁ ପଥାଚାରୀଙ୍କ ନିମନ୍ତେ ଉପର ପାଦଚଲା ପୋଲ (Foot Over-bridge)ନିର୍ମାଣ ଆବଶ୍ୟକ ।

(ଙ) ଅତିବ୍ୟସ୍ତ ସମୟରେ ପ୍ରତ୍ୟେକ ରାସ୍ତାରେ ଯାନବାହନର ପରିମାଣକୁ ଦୃଷ୍ଟିରେ ରଖି ପ୍ରତ୍ୟେକ ଛକମାନଙ୍କରେ ଯାତାୟତ ସଙ୍କେତର ସମୟ ଅବଧି ସଠିକ୍ ନିର୍ଦ୍ଧାରଣ ହେବା ଆବଶ୍ୟକ । ଫଳରେ, ଯାନବାହନ ଚଳାଚଳରେ ଅଯଥା ବିଳମ୍ବ ତଥା ତଦ୍‌ଜନିତ ଯାତାୟତକାରୀଙ୍କ ସାମୟିକ ହିଂସାତ୍ମକ କାର୍ଯ୍ୟକଳାପ ରୋକାଯାଇପାରିବ ।

ତୁମ ପାଇଁ କାମ

ସାଧାରଣ ପରିବହନ ବ୍ୟବସ୍ଥା ପ୍ରତି ଲୋକଙ୍କ ମଧ୍ୟରେ ଆଗ୍ରହ ସୃଷ୍ଟି କରିବା ପାଇଁ ବିଭିନ୍ନ ସ୍ଲୋଗାନ ଲେଖିବା ଓ ପୋଷ୍ଟର ପ୍ରତିଯୋଗିତାର ଆୟୋଜନ ।

ବୟସ୍କ, ଦିବ୍ୟାଙ୍ଗ ତଥା ଅଳ୍ପବୟସ୍କ ମାନଙ୍କ ପାଇଁ ରାସ୍ତାରେ ଗମନାଗମନର ସ୍ୱତନ୍ତ୍ର ଆବଶ୍ୟକତାର ଅବଧାରଣା :

1. ସମାଜର ବିଭିନ୍ନ ବର୍ଗର ଲୋକମାନଙ୍କର ତଥା ଦିବ୍ୟାଙ୍ଗବ୍ୟକ୍ତିମାନଙ୍କର ଆବଶ୍ୟକତାକୁ ଆଖି ଆଗରେ ରଖି ସମସ୍ତେ ଯେପରି ସବୁ ପ୍ରକାର ରାସ୍ତା, ରେଳଷ୍ଟେସନ, ପାଦଚଲା ରାସ୍ତା ବ୍ୟବହାର କରି ଖୁବ୍ ସହଜ ଓ ନିରାପଦରେ ସେମାନଙ୍କର ଲକ୍ଷ୍ୟସ୍ଥଳରେ ପହଞ୍ଚିପାରିବେ, ସେଥିପାଇଁ ଉପଯୁକ୍ତ ଯୋଜନା ପ୍ରଣୟନ କରି ସହରାଞ୍ଚଳରେ ଭିତ୍ତିଭୂମିର ବିକାଶ ଉପରେ ଗୁରୁତ୍ୱ ଦିଆଯିବା ଆବଶ୍ୟକ। ଦିବ୍ୟାଙ୍ଗମାନଙ୍କ ଗମନାଗମନ ପାଇଁ ର୍‍ୟାମ୍ପର ବ୍ୟବସ୍ଥା କରାଯିବା ଦରକାର ।

2.**ପାଦଚଲା ପୋଲ** (Foot bridge) ଗୁଡ଼ିକ ଯେପରି ନଭାଙ୍ଗିବ ଏବଂ ରାସ୍ତାରେ ଯେପରି ଦଳାଚକଟା ନ ହେବ, ସେଥିପାଇଁ ବସଷ୍ଟାଣ୍ଡ, ବିମାନଘାଟୀ ଓ ରେଳଷ୍ଟସନକୁ ଯାତ୍ରୀମାନଙ୍କର ଗମନାଗମନ ଏବଂ ସେମାନଙ୍କର ଜିନିଷପତ୍ର ସୁବିଧାରେ ନେବା ଆଣିବା କରିବା ପାଇଁ ଆବଶ୍ୟକ ପଦକ୍ଷେପ ଗ୍ରହଣ କରାଯିବା ଆବଶ୍ୟକ ।

ବିକାଶ ଜଣେ ବ୍ୟକ୍ତିକୁ ଅଧିକ ପୁଞ୍ଜି ସହିତ ଆର୍ଥିକ ସ୍ୱଚ୍ଛଳତା ପ୍ରାପ୍ତ ପାଇଁ ସୁଯୋଗ ଦେଇଥାଏ । ଏହା ଫଳରେ ସହରାଞ୍ଚଳରେ ଗାଡ଼ିମୋଟରର ସଂଖ୍ୟା ବଢ଼ିବା ସହିତ ବେପରୁଆ ଗାଡ଼ିଚାଳକଙ୍କ ସଂଖ୍ୟା ଓ ସ୍ୱଚ୍ଛଳ ବ୍ୟକ୍ତିଙ୍କ ଅପ୍ରାପ୍ତବୟସ୍କ ଗାଡ଼ିଚାଳକ ପିଲାଙ୍କ ସଂଖ୍ୟା ବୃଦ୍ଧିପାଇଛି । ମଦ୍ୟପାନ ଜନିତ ଗାଡ଼ିଚାଳନାର ମାତ୍ରା ଯଥେଷ୍ଟ ବଢ଼ିଯାଇଛି । ଫଳରେ ଆମ ଦେଶରେ ଗାଡ଼ି ଦୁର୍ଘଟଣା ଉଦ୍‌ବେଗଜନିତ ଭାବେ ବୃଦ୍ଧି ପାଇଛି । ଏ ପ୍ରକାର ଅଘଟଣକୁ ଏଡ଼ାଇବା ପାଇଁ କଠୋର ତଥା ଦୃଷ୍ଟାନ୍ତମୂଳକ ଦଣ୍ଡ ବ୍ୟବସ୍ଥା ଗ୍ରହଣ କରାଯିବା ସହିତ ଜନସାଧାରଣଙ୍କ ମଧ୍ୟରେ ସଚେତନତା ଏକାନ୍ତ ଜରୁରୀ । ଏହାଯୋଗୁଁ ଅବାଞ୍ଛିତ ଧନଜୀବନ ହାନି ବହୁମାତ୍ରାରେ ରୋକାଯାଇପାରିବ ।

ପ୍ରଶ୍ନାବଳୀ

1. ନିମ୍ନଲିଖିତ ପ୍ରଶ୍ନଗୁଡ଼ିକର ଉତ୍ତର ଦିଅ ।

(i) ପରିବହନ ଦ୍ୱାରା ଆମର କି କି ଉପକାର ହେଉଛି ବର୍ଣ୍ଣନା କର ।

(ii) ଭାରତୀୟ ସଡ଼କ ପଥର ଶ୍ରେଣୀ ବିଭାଗ କର ।

(iii) ଭାରତୀୟ ରାଜପଥ କାହାକୁ କୁହାଯାଏ ? ଜାତୀୟ ରାଜପଥର ଏକ ବିବରଣୀ ଦିଅ ।

(iv) 'ସୀମାନ୍ତ ସଡ଼କ ସଂସ୍ଥା' ସମ୍ବନ୍ଧରେ ଏକ ବିବରଣୀ ଦିଅ ।

(v) ସଡ଼କ ପଥର ଉନ୍ନତି ପାଇଁ ଭାରତ ସରକାର କେଉଁ କେଉଁ ପଦକ୍ଷେପ ନେଉଛନ୍ତି ସେ ସମ୍ବନ୍ଧରେ ବର୍ଣ୍ଣନା କର ।

(vi) ଭାରତୀୟ ରେଳପଥ ସମ୍ବନ୍ଧରେ ବର୍ଣ୍ଣନା କର ।

(vii) ଭାରତର ପାଇପ୍‌ଲାଇନ୍ ପରିବହନ ସମ୍ବନ୍ଧରେ ସୂଚନା ଦିଅ ।

(viii) ଭାରତୀୟ ବାୟୁସେବା ସମ୍ବନ୍ଧରେ ଉଲ୍ଲେଖ କର ।

(ix) ଭାରତୀୟ ବାଣିଜ୍ୟ ପଥର ଏକ ବିବରଣୀ ଦିଅ ।

2. ନିମ୍ନଲିଖିତ ପ୍ରଶ୍ନଗୁଡ଼ିକର ଉତ୍ତର ସଂକ୍ଷେପରେ ଲେଖ -

(i) 'ପରିବହନ' କହିଲେ କ'ଣ ବୁଝାଯାଏ ?

(ii) ଯୋଗାଯୋଗ କେଉଁଥିପାଇଁ ଗୁରୁତ୍ୱପୂର୍ଣ୍ଣ ?

(iii) ଯୋଗାଯୋଗର 4ଟି ମାଧ୍ୟମର ନାମଲେଖ ?

(iv) ଗଣମାଧ୍ୟମ କହିଲେ କ'ଣ ବୁଝ ?

(v) ରାଜ୍ୟ ରାଜପଥ କାହାକୁ କୁହାଯାଏ ?

(vi) ତିନୋଟି ଗଣମାଧ୍ୟମର ନାମ ଲେଖ ।

(vii) ଭାରତରେ କେତୋଟି ରେଳବାଇ ମଣ୍ଡଳ ଅଛି ?

(viii) ଭାରତରେ ଜଳପରିବହନ ପାଇଁ ଉପଯୁକ୍ତ ଦୁଇଟି ନଦୀର ନାମ ଲେଖ ।

(ix) ପରିବହନ କିପରି ଦେଶର ଏକତା ଭାବକୁ ଦୃଢ଼ କରେ ।

(x) ଭାରତର ପୂର୍ବଉପକୂଳରେ ଅବସ୍ଥିତ 4ଟି ପ୍ରଧାନ ବନ୍ଦରର ନାମ ଲେଖ ।

(xi) ହିମାଚଳ ପ୍ରଦେଶର ମନାଲି ଠାରୁ ଲାଦାଖର ଲେହ ପର୍ଯ୍ୟନ୍ତ ବିସ୍ତୃତ ସଡ଼କ ପଥ କେଉଁ ସଡ଼କ ଶ୍ରେଣୀ ଭୁକ୍ତ ?

(xii) ସ୍ୱର୍ଣ୍ଣ ଚତୁର୍ଭୁଜ କହିଲେ କ'ଣ ବୁଝ ?

(xiii) ଦେଶର ଥିବା 6ଟି ଆନ୍ତର୍ଜାତୀୟ ବିମାନ ବନ୍ଦରର ନାମ ଲେଖ ।

(xiv) ଭାରତରେ ଥିବା 4ଟି ସମ୍ବାଦ ସରବରାହ ସଂସ୍ଥାର ନାମ ଲେଖ ।

(xv) ଭାରତରୁ ରପ୍ତାନୀ ହେଉଥିବା 4ଟି ଦ୍ରବ୍ୟର ନାମ ଲେଖ ।

(xvi) ବାଣିଜ୍ୟକ ଉଦ୍‌ବୃତ୍ତି କ'ଣ ?

(xvii) ଭାରତରେ ବର୍ହିବାଣିଜ୍ୟ କେଉଁ ଦେଶମାନଙ୍କ ସହ ହେଉଛି ତାର ଏକ ସୂଚନା ଦିଅ ।

(xviii) ସର୍ବପୁରାତନ ଜାତୀୟ ରାଜପଥର ନାମ ଲେଖ ।

(xix) କେଉଁ କେଉଁ ରାଜ୍ୟରେ ହଳଦିଆ, ତୁତିକୋରିନ୍ ଓ କାଣ୍ଡଲା ବନ୍ଦର ଗୁଡ଼ିକ ଅବସ୍ଥିତ ଲେଖ ।

3. ପାର୍ଥକ୍ୟ ଦଶାଅ -

(a) ପରିବହନ ଓ ଯୋଗାଯୋଗ

(b) ରେଳ ପଥ ଓ ସଡ଼କ ପଥ

(c) ଆମଦାନି ଓ ରପ୍ତାନୀ

(d) ଅନ୍ତଃବାଣିଜ୍ୟ ଓ ବର୍ହିବାଣିଜ୍ୟ

(e) ବ୍ରଡ଼ଗେଜ୍ ଓ ମିଟର ଗେଜ୍

(f) ଆଭ୍ୟନ୍ତରୀଣ ଜଳପଥ ଓ ସାମୁଦ୍ରିକ ଜଳପଥ

(g) ଇଣ୍ଡିଆନ୍ ଏୟାରଲାଇନସ୍ ଓ ଏୟାର ଇଣ୍ଡିଆ

4. କାରଣ ଦର୍ଶାଅ -

(i) ପରିବହନ ବ୍ୟବସ୍ଥାକୁ ଦେଶର ଜୀବନରେଖା କୁହାଯାଏ ।

(ii) ଅଗମ୍ୟ ଅଞ୍ଚଳରେ ବାୟୁ ପରିବହନ ଗୁରୁତ୍ୱପୂର୍ଣ୍ଣ ।

(iii) ପାଇପଲାଇନ୍ ଦ୍ୱାରା ପେଟ୍ରୋଲିୟମ ପରିବହନ ସୁବିଧା ଜନକ ।

(iv) ସଡ଼କ ପଥ ସମସ୍ତ ପରିବହନ ବ୍ୟବସ୍ଥା ମଧ୍ୟରେ ଅଧିକ ଗୁରୁତ୍ୱପୂର୍ଣ୍ଣ ।

5. 'କ' ସ୍ତମ୍ଭରେ ଦିଆଯାଇଥିବା ରେଳବାଇମଣ୍ଡଳଗୁଡ଼ିକୁ 'ଖ' ସ୍ତମ୍ଭରେ ଦିଆଯାଇଥିବା ସଂପୃକ୍ତ ପ୍ରଧାନ କାର୍ଯ୍ୟାଳୟ ସହ ଯୋଡ଼ିଲେଖ ।

'କ' ସ୍ତମ୍ଭ	'ଖ' ସ୍ତମ୍ଭ
(କ) ପୂର୍ବ-ଉପକୂଳ ରେଳପଥ	ଗୋରଖପୁର
(ଖ) ପୂର୍ବ ରେଳପଥ	ମାଲିଗାଓଁ
(ଗ) ଉତ୍ତର-ପୂର୍ବରେଳପଥ	ବିଳାସପୁର
(ଘ) ଉତ୍ତର-ପୂର୍ବସୀମାନ୍ତ ରେଳପଥ	କୋଲକାତା
(ଙ) ଦକ୍ଷିଣ-ପୂର୍ବକେନ୍ଦ୍ରୀୟ ରେଳପଥ	ଭୁବନେଶ୍ୱର
(ଚ) ଦକ୍ଷିଣ-ଉପକୂଳ ରେଳପଥ	ବିଶାଖାପାଟଣା

6. ଭାରତର ଏକ ରେଖାଙ୍କିତ ମାନଚିତ୍ରରେ ନିମ୍ନଲିଖିତ ସ୍ଥାନଗୁଡ଼ିକ ଦର୍ଶାଅ ।

(a) ଦିଲ୍ଲୀ ଓ ମୁମ୍ବାଇ ମଧ୍ୟରେ ଭୋପାଳ ଦେଇ ଯାଇଥିବା ଜାତୀୟ ରାଜପଥ

(b) ଉତ୍ତର-ଦକ୍ଷିଣ ଅଳିନ୍ଦ ଦ୍ରୁତ ଜାତୀୟ ରାଜପଥ

(c) ଏଲ୍ଲାହାବାଦ ଓ କୋଲକାତା ମଧ୍ୟରେ ଥିବା ଅନ୍ତର୍ଦ୍ଦେଶୀୟ ଜଳପଥ

(d) କୋଚି, ବିଶାଖାପାଟଣା, ନବସେବା ଓ ମାଙ୍ଗାଲୋର ଓ କୋଲକାତା ବନ୍ଦର

7. ବନ୍ଧନୀ ମଧ୍ୟରେ ଦିଆଯାଇଥିବା ସମ୍ଭାବ୍ୟ ଉତ୍ତରଗୁଡ଼ିକରୁ ଠିକ୍ ଉତ୍ତରଟି ବାଛି ଶୂନ୍ୟସ୍ଥାନ ପୂରଣ କର ।

(a) ବ୍ରଡ଼ଗେଜ ରେଳରାସ୍ତାରେ ଦୁଇଟି ଧାରଣା ମଧ୍ୟରେ ବ୍ୟବଧାନ ---- ମିଟର ଅଟେ । (0.72, 1.6, 1.67, 1.76)

(b) ଦକ୍ଷିଣ-ପଶ୍ଚିମ ରେଳପଥର ମୁଖ୍ୟ କାର୍ଯ୍ୟାଳୟ ---- ଠାରେ ଅବସ୍ଥିତ । (ମୁମ୍ବାଇ, ଜୟପୁର, ବିଳାସପୁର, ହୁବଳି)

(c) ଭାରତର ଦକ୍ଷିଣ ଆମେରିକୀୟ ଦେଶମାନଙ୍କ ସହିତ ---- ସମୁଦ୍ରପଥ ଦେଇ ବାଣିଜ୍ୟ କାରବାର ହୁଏ ।
(ସିଙ୍ଗାପୁର, ଉତ୍ତମାଶା ଅନ୍ତରୀପ, ସୁଏଜ୍ କେନାଲ, ଅଷ୍ଟ୍ରେଲିଆ ପଥ)

(d) ଭାରତରେ ---- ଟି ପ୍ରଧାନ ବନ୍ଦର ଅଛି । (10, 11, 12, 13)

(e) ଚଳଚିତ୍ର ନିର୍ମାଣରେ ଭାରତର ସ୍ଥାନ ପୃଥିବୀରେ ---- ଅଟେ । (ପ୍ରଥମ, ଦ୍ୱିତୀୟ, ତୃତୀୟ, ଚତୁର୍ଥ)

(f) ଭାରତରେ ---- ଭାଷାରେ ସବୁଠାରୁ ଅଧିକ ସମ୍ବାଦପତ୍ର ପ୍ରକାଶ ପାଏ । (ଇଂରାଜୀ, ହିନ୍ଦୀ, ବଙ୍ଗାଳୀ, ମାଲୟାଲମ୍)

✳ ✳ ✳